KEMENTERIAN KEUANGAN REPUBLIK INDONESIA
DIREKTORAT JENDERAL PAJAK

SURAT EDARAN
NOMOR SE- 16 /PJ/2022

TENTANG
PETUNJUK TEKNIS PEMBENTUKAN BASIS DATA SPASIAL OBJEK PAJAK
PAJAK BUMI DAN BANGUNAN SEKTOR PERHUTANAN

Yth. 1. Pejabat Eselon II di lingkungan Kantor Pusat Direktorat Jenderal Pajak;
2. Kepala Kantor Wilayah; dan
3. Kepala Kantor Pelayanan Pajak,
di lingkungan Direktorat Jenderal Pajak.

A. Umum

Dalam rangka mendukung pembangunan peta digital Direktorat Jenderal Pajak (DJP *Digital Map*) yang merupakan salah satu bagian dari Rencana Strategis Direktorat Jenderal Pajak (DJP) sesuai dengan Keputusan Direktur Jenderal Pajak Nomor KEP-390/PJ/2020 tentang Pedoman Tata Kelola dan Implementasi Rencana Strategis Direktorat Jenderal Pajak Tahun 2020 – 2024, telah disusun serangkaian rencana untuk pembangunan DJP *Digital Map*. DJP *Digital Map* merupakan sebuah sistem yang berupa aplikasi yang berdiri sendiri, dan juga menyediakan *service* data spasial ke sistem lainnya, termasuk interoperabilitas ke Sistem Inti Administrasi Perpajakan (SIAP).

Pada prinsipnya, pembangunan DJP *Digital Map* membutuhkan ketersediaan data dan modul aplikasi. Data yang dibutuhkan dapat berupa data internal dan eksternal, data spasial PBB Sektor Perkebunan, Perhutanan, Pertambangan Minyak dan Gas Bumi, Pertambangan untuk Pengusahaan Panas Bumi, dan Pertambangan Mineral dan Batu Bara (P5), data *geotagging*, data pendukung monografi fiskal, dan data tematik dari proses bisnis yang ada di DJP, seperti pengawasan dan penegakan hukum. DJP *Digital Map* membutuhkan peta dasar *(base map),* SIG PBB Sektor P5, peta tematik dari proses bisnis DJP, *Assignment* Wajib Pajak, dan Kegiatan Pengumpulan Data (KPD), serta sarana interoperabilitas ke SIAP. Sebagai dasar pembentukan aplikasi dimaksud, diperlukan dukungan regulasi, antara lain regulasi mengenai pembentukan basis data spasial objek PBB Sektor P5 untuk menjadi landasan pembangunan DJP *Digital Map* modul SIG PBB Sektor P5.

Sehubungan dengan hal tersebut di atas dan untuk memenuhi kebutuhan pembangunan DJP *Digital Map* modul SIG PBB Sektor Perhutanan yang membutuhkan basis data spasial PBB Sektor Perhutanan yang saat ini belum dimiliki DJP, perlu menetapkan Surat Edaran Direktur Jenderal Pajak tentang Petunjuk Teknis Pembentukan Basis Data Spasial Objek Pajak Pajak Bumi dan Bangunan Sektor Perhutanan.

Basis ...

Basis data spasial objek PBB Sektor Perhutanan diperlukan untuk menentukan tindak lanjut dalam pengawasan kepatuhan perpajakan, pengambilan keputusan terkait perpajakan di Sektor Perhutanan, dan analisis spasial untuk penggalian potensi perpajakan. Terkait dengan fungsi pengawasan kepatuhan perpajakan, basis data spasial tersebut dapat digunakan antara lain untuk:

a. permintaan klarifikasi data objek pajak dalam Surat Pemberitahuan Objek Pajak (SPOP) antara lain data luasan, baik luasan kawasan, luasan jenis areal, dan luasan berdasarkan jenis tanaman; dan
b. permintaan penjelasan data terkait kesesuaian elemen data dalam Surat Pemberitahuan (SPT) Tahunan Pajak Penghasilan dengan hasil analisis atas SPOP dan dokumen pendukung isian SPOP yang disampaikan oleh Wajib Pajak.

Basis data spasial objek PBB Sektor Perhutanan yang berkualitas diperlukan agar tercapai tertib administrasi penatausahaan objek pajak serta optimalisasi penerimaan PBB Sektor Perhutanan. Oleh karena itu, penetapan Surat Edaran Direktur Jenderal ini diperlukan untuk memberikan petunjuk sehingga pembentukan basis data spasial Objek Pajak PBB Sektor Perhutanan dapat dilakukan secara efektif dan efisien.

B. Maksud dan Tujuan

1. Maksud
   Surat Edaran Direktur Jenderal ini dimaksudkan untuk memberikan petunjuk teknis dalam pembentukan basis data spasial Objek Pajak PBB Sektor Perhutanan.
2. Tujuan
   Surat Edaran Direktur Jenderal ini bertujuan untuk menciptakan keseragaman prosedur dalam pembentukan basis data spasial Objek Pajak PBB Sektor Perhutanan sehingga dapat dimanfaatkan untuk pengawasan kepatuhan perpajakan, pengambilan keputusan terkait perpajakan di Sektor Perhutanan, dan analisis spasial untuk penggalian potensi perpajakan.

C. Ruang Lingkup

Ruang lingkup Surat Edaran Direktur Jenderal ini meliputi:

1. pengertian;
2. ketentuan umum;
3. pengumpulan peta;
4. pengolahan peta; dan
5. ketentuan lain-lain.

D. Dasar

1. Undang-Undang Nomor 6 Tahun 1983 tentang Ketentuan Umum dan Tata Cara Perpajakan sebagaimana telah beberapa kali diubah terakhir dengan Undang-Undang Nomor 7 Tahun 2021 tentang Harmonisasi Peraturan Perpajakan;
2. Undang-Undang Nomor 12 Tahun 1985 tentang Pajak Bumi dan Bangunan sebagaimana telah diubah dengan Undang-Undang Nomor 12 Tahun 1994 tentang Perubahan atas Undang-Undang Nomor 12 Tahun 1985 tentang Pajak Bumi dan Bangunan;
3. Peraturan Menteri Keuangan Nomor 256/PMK.03/2014 tentang Tata Cara Pemeriksaan dan Penelitian Pajak Bumi dan Bangunan;
4. Peraturan Menteri Keuangan Nomor 228/PMK.03/2017 tentang Rincian Jenis Data dan Informasi serta Tata Cara Penyampaian Data dan Informasi yang berkaitan dengan Perpajakan;

5. Peraturan ...

5. Peraturan Menteri Keuangan Nomor 186/PMK.03/2019 tentang Klasifikasi Objek Pajak dan Tata Cara Penetapan Nilai Jual Objek Pajak Pajak Bumi dan Bangunan;
6. Peraturan Menteri Keuangan Nomor 210/PMK.01/2017 tentang Organisasi dan Tata Kerja Instansi Vertikal Direktorat Jenderal Pajak sebagaimana telah diubah dengan Peraturan Menteri Keuangan Nomor 184/PMK.01/2020 tentang Perubahan atas Peraturan Menteri Keuangan Nomor 210/PMK.01/2017 tentang Organisasi dan Tata Kerja Instansi Vertikal Direktorat Jenderal Pajak;
7. Peraturan Menteri Keuangan Nomor 48/PMK.03/2021 tentang Tata Cara Pendaftaran, Pelaporan, dan Pendataan Objek Pajak Pajak Bumi dan Bangunan;
8. Peraturan Direktur Jenderal Pajak Nomor PER-29/PJ/2016 tentang Tata Cara Pemetaan Objek Pajak Pajak Bumi dan Bangunan;
9. Peraturan Direktur Jenderal Pajak Nomor PER-08/PJ/2019 tentang Pemberian, Penyesuaian, dan Penghapusan Nomor Objek Pajak Pajak Bumi dan Bangunan; dan
10. Peraturan Direktur Jenderal Pajak Nomor PER-23/PJ/2021 tentang Surat Pemberitahuan Objek Pajak Pajak Bumi dan Bangunan.

E. Materi

1. Pengertian

   Dalam Surat Edaran Direktur Jenderal ini, yang dimaksud dengan:

   a. Data Spasial adalah data hasil pengukuran, pencatatan, dan pencitraan terhadap suatu unsur keruangan yang berada di bawah, pada, atau di atas permukaan bumi dengan posisi keberadaannya mengacu pada sistem koordinat nasional.
   b. Analisis Spasial adalah teknik ataupun proses yang melibatkan sejumlah fungsi perhitungan matematis atas data spasial untuk memperoleh nilai tambah, ekstraksi serta informasi baru yang beraspek spasial dalam rangka membantu pengambilan keputusan.
   c. Objek Pajak PBB Sektor Perhutanan adalah bumi dan/atau bangunan yang berada di kawasan perhutanan.
   d. Kawasan Perhutanan yang selanjutnya disebut Kawasan adalah areal yang meliputi:
      1) areal sebagaimana tercantum dalam Izin Usaha Pemanfaatan Hasil Hutan Kayu dalam Hutan Alam (IUPHHK-HA) dan/atau Izin Usaha Pemanfaatan Hasil Hutan Bukan Kayu dari Hutan Alam (IUPHHBK-HA), Izin Usaha Pemanfaatan Hasil Hutan Kayu Restorasi Ekosistem dalam Hutan Alam (IUPHHK-RE), Izin Usaha Pemanfaatan Hasil Hutan Kayu pada Hutan Tanaman Industri dalam Hutan Tanaman pada Hutan Produksi (IUPHHK-HTI), dan/atau IUPHHBK-HT, atau penugasan dari pemerintah kepada Perusahaan Pemegang Izin Usaha Pemanfaatan Hasil Hutan Bukan Kayu dari Hutan Tanaman pada Hutan Produksi (IUPHHBK-HT) Kehutanan Negara (Perum Perhutani); dan
      2) areal di luar areal sebagaimana dimaksud pada angka 1) yang merupakan satu kesatuan yang digunakan untuk kegiatan usaha perhutanan dan secara fisik tidak terpisahkan.
   e. Hutan Produksi adalah kawasan hutan yang mempunyai fungsi pokok memproduksi hasil hutan.
   f. Hutan Alam adalah suatu lapangan yang bertumbuhan pohon-pohon alami yang secara keseluruhan merupakan persekutuan hidup alam hayati beserta alam lingkungannya.
   g. Hutan Tanaman adalah hutan yang dibangun dalam rangka meningkatkan potensi dan kualitas Hutan Produksi dengan menerapkan silvikultur intensif.

h. Izin ...

h. Izin Usaha Pemanfaatan Hasil Hutan Kayu dalam Hutan Alam yang selanjutnya disingkat IUPHHK-HA, yang sebelumnya disebut Hak Pengusahaan Hutan (HPH) adalah izin memanfaatkan Hutan Produksi yang kegiatannya terdiri dari penebangan, pengangkutan, penanaman, pemeliharaan, pengamanan, pengolahan, dan pemasaran hasil hutan kayu.

i. Izin Usaha Pemanfaatan Hasil Hutan Kayu pada Hutan Tanaman Industri dalam Hutan Tanaman pada Hutan Produksi yang selanjutnya disingkat IUPHHK-HTI yang sebelumnya disebut Hak Pengusahaan Hutan Tanaman (HPHT), Hak Pengusahaan Hutan Tanaman Industri (HPHTI) atau Izin Usaha Pemanfaatan Hasil Hutan Kayu pada Hutan Tanaman (IUPHHK-HTI) adalah izin usaha untuk membangun Hutan Tanaman pada Hutan Produksi yang dibangun oleh kelompok industri untuk meningkatkan potensi dan kualitas Hutan Produksi dalam rangka memenuhi kebutuhan bahan baku industri.

j. Izin Usaha Pemanfaatan Hasil Hutan Kayu Restorasi Ekosistem dalam Hutan Alam yang selanjutnya disingkat IUPHHK-RE adalah izin usaha yang diberikan untuk membangun kawasan dalam Hutan Alam pada Hutan Produksi yang memiliki ekosistem penting sehingga dapat dipertahankan fungsi dan keterwakilannya melalui kegiatan pemeliharaan, perlindungan dan pemulihan ekosistem hutan termasuk penanaman, pengayaan, penjarangan, penangkaran satwa, pelepasliaran flora dan fauna untuk mengembalikan unsur hayati (flora dan fauna) serta unsur non hayati (tanah, iklim, dan topografi) pada suatu kawasan kepada jenis yang asli, sehingga tercapai keseimbangan hayati dan ekosistemnya.

k. Izin Usaha Pemanfaatan Hasil Hutan Bukan Kayu dari Hutan Alam pada Hutan Produksi yang selanjutnya disebut IUPHHBK-HA adalah izin usaha yang diberikan untuk memanfaatkan hasil hutan bukan kayu dari Hutan Alam pada Hutan Produksi melalui kegiatan pengayaan, pemeliharaan, perlindungan, pemanenan, pengamanan, dan pemasaran hasil.

l. Izin Usaha Pemanfaatan Hasil Hutan Bukan Kayu dari Hutan Tanaman pada Hutan Produksi yang selanjutnya disebut IUPHHBK-HT adalah izin usaha yang diberikan untuk memanfaatkan hasil hutan bukan kayu dari Hutan Tanaman pada Hutan Produksi melalui kegiatan penyiapan lahan, pembibitan, penanaman, pemeliharaan, pemanenan, pengamanan, dan pemasaran hasil.

m. Surat Pemberitahuan Objek Pajak yang selanjutnya disingkat SPOP adalah surat yang digunakan oleh Wajib Pajak untuk melaporkan data objek pajak menurut ketentuan Undang-Undang PBB yang dilampiri dengan lampiran SPOP yang merupakan bagian tidak terpisahkan dengan SPOP.

n. Peta adalah suatu gambaran dari unsur-unsur alam dan/atau buatan manusia, yang berada di atas atau di bawah permukaan bumi yang digambarkan pada suatu bidang datar dengan skala tertentu.

o. Peta Kerja adalah Peta sebagai lampiran SPOP yang disampaikan oleh Wajib Pajak pada saat melaporkan SPOP yang menunjukkan batas dan pembagian blok serta rencana dan realisasi kegiatan Wajib Pajak yang dibedakan berdasarkan tahun.

p. Pengumpulan Peta adalah kegiatan untuk memperoleh, mengumpulkan, melengkapi, dan menatausahakan Peta objek pajak PBB.

q. Pengolahan Peta adalah kegiatan menyesuaikan Peta yang dikumpulkan menjadi Peta sesuai standar yang telah ditentukan dan mengunggahnya pada aplikasi yang telah disediakan oleh Direktorat Jenderal Pajak.

r. Pemeriksaan ...

r. Pemeriksaan adalah serangkaian kegiatan mencari, menghimpun, dan mengolah data, keterangan, dan/atau bukti, yang dilaksanakan secara objektif dan profesional berdasarkan suatu standar pemeriksaan untuk menguji kepatuhan pemenuhan kewajiban PBB dan/atau untuk tujuan lain dalam rangka melaksanakan ketentuan peraturan perundang-undangan PBB.
s. Surat Pernyataan adalah Surat Pernyataan Belum Dapat Melampirkan Dokumen Pendukung SPOP.
t. Surat Konfirmasi adalah Surat Konfirmasi atas Surat Pernyataan Wajib Pajak.
u. Penilai Pajak adalah Pejabat Fungsional Penilai Pajak, Pejabat Fungsional Asisten Penilai Pajak, dan Petugas Penilai Pajak.
v. Tahun Tanam adalah tahun saat dilakukan penanaman pada Hutan Tanaman.
w. Tahun Tebang adalah tahun saat dilakukan penebangan pada Hutan Alam.
x. Sistem Referensi Koordinat atau *Coordinate Reference System* yang selanjutnya disingkat CRS adalah sistem koordinat lokal, regional, atau global yang digunakan untuk menentukan lokasi suatu entitas geografis.
y. Registrasi Peta adalah suatu proses pemberian koordinat Peta pada hasil pemindaian (*scan*) sesuai dengan koordinat di muka bumi.
z. *Layer* adalah lapisan Peta yang memuat informasi dari Peta, yang dapat berupa poligon, garis, titik, teks, simbol, dan lain-lain.
aa. *Layer* Izin adalah *Layer* Peta yang menunjukkan batas perizinan yang dimiliki Wajib Pajak.
bb. *Layer* Kawasan adalah *Layer* Peta yang menggambarkan kawasan perhutanan yang dimanfaatkan Wajib Pajak.
cc. *Layer* Areal adalah *Layer* Peta yang menunjukkan pembagian areal kerja berdasarkan Rencana Kerja Tahunan dalam kawasan perhutanan.
dd. *Layer* Areal Tanam adalah *Layer* Peta yang menunjukkan pembagian areal kerja berdasarkan jenis tanaman dalam kawasan perhutanan tanaman.
ee. *Layer* Rencana Kerja Tahunan yang selanjutnya disebut *Layer* RKT adalah *Layer* Peta yang menunjukkan batas dan pembagian blok serta rencana dan realisasi kegiatan Wajib Pajak yang dibedakan berdasarkan tahun.
ff. Kepala Kantor Wilayah Direktorat Jenderal Pajak yang selanjutnya disebut Kepala Kanwil DJP adalah Kepala Kanwil DJP yang mengadministrasikan Objek Pajak PBB Sektor Perhutanan.
gg. Kepala Kantor Pelayanan Pajak selanjutnya disebut Kepala KPP adalah Kepala KPP yang mengadministrasikan Objek Pajak PBB Sektor Perhutanan.

2. Ketentuan Umum
   a. Kegiatan pembentukan basis Data Spasial Objek Pajak PBB Sektor Perhutanan dilaksanakan melalui:
      1) Pengumpulan Peta; dan
      2) Pengolahan Peta.
   b. Sumber data pembentukan basis Data Spasial Objek Pajak PBB Sektor Perhutanan meliputi:
      1) data internal berupa Peta dari Wajib Pajak yang disampaikan melalui SPOP; dan
      2) data eksternal berupa Peta dari Instansi Pemerintah, Lembaga, Asosiasi, dan Pihak Lain (ILAP).

c. Terhadap ...

c. Terhadap data Peta Wajib Pajak yang disampaikan melalui SPOP sebagaimana dimaksud dalam huruf b angka 1) dilakukan pengolahan sesuai standar sehingga diperoleh data berupa:
   1) data atributif dari isian SPOP; dan
   2) *Layer* Peta yang meliputi *Layer* Izin, *Layer* Kawasan, *Layer* Areal, *Layer* Areal Tanam, dan *Layer* RKT.

d. Pengumpulan Peta dan Pengolahan Peta dilakukan oleh Kantor Pelayanan Pajak (KPP), Kantor Wilayah Direktorat Jenderal Pajak (Kanwil DJP), dan Kantor Pusat Direktorat Jenderal Pajak (KPDJP) dalam hal ini Direktorat Ekstensifikasi dan Penilaian.

e. Direktorat Ekstensifikasi dan Penilaian mengoordinasikan:
   1) Pengumpulan Peta dan Pengolahan Peta yang dilakukan oleh KPP melalui Kanwil DJP; dan
   2) Pengumpulan Peta dan Pengolahan Peta yang diperoleh melalui ILAP sebagaimana diatur dalam peraturan perundang-undangan mengenai perolehan data melalui ILAP.

f. Direktorat Ekstensifikasi dan Penilaian berkoordinasi dengan Direktorat Data dan Informasi Perpajakan serta Direktorat Teknologi Informasi dan Komunikasi untuk membangun aplikasi Basis Data Spasial PBB.

g. Aplikasi sebagaimana dimaksud dalam huruf f dapat diakses oleh unit vertikal DJP dalam rangka pengawasan perpajakan dan/atau Pemeriksaan Wajib Pajak sektor perhutanan, serta dimanfaatkan untuk:
   1) penggambaran *Layer* Kawasan (wilayah terluar) Objek Pajak PBB Sektor Perhutanan;
   2) tematik berdasarkan *Layer* Objek Pajak PBB Sektor Perhutanan, berupa data lokasi, Wajib Pajak, perizinan, detail areal, areal tanam, dan hasil produksi;
   3) pemadanan Nomor Objek Pajak Peta yang disampaikan Wajib Pajak dengan Peta dari ILAP; dan
   4) menampilkan data historis ketetapan PBB.

3. Pengumpulan Peta
   a. Dalam rangka pembentukan basis Data Spasial Objek Pajak PBB Sektor Perhutanan, DJP dapat memperoleh Peta yang bersumber dari:
      1) Wajib Pajak melalui penyampaian SPOP PBB Sektor Perhutanan;
      2) Wajib Pajak pada saat dilakukan kegiatan pengawasan dan/atau Pemeriksaan;
      3) Wajib Pajak pada saat mengajukan keberatan, banding, dan pengurangan; dan
      4) ILAP.
   b. Pengumpulan Peta dilakukan di unit kerja DJP sebagai berikut:
      1) KPP
         a) Pengumpulan Peta melalui penyampaian SPOP PBB Sektor Perhutanan.
            (1) Kepala KPP melakukan beberapa hal sebagai berikut:
               (a) mengidentifikasi ketersediaan Peta Kerja dalam SPOP yang disampaikan oleh Wajib Pajak;
               (b) merekapitulasi Peta Objek Pajak PBB Sektor Perhutanan melalui pembuatan Daftar Ketersediaan Peta Objek Pajak serta Laporan Perkembangan Pengumpulan Peta dan Pengolahan Peta yang dibuat paling lambat 10 (sepuluh) hari, sejak:

i. berakhirnya ...

i. berakhirnya jangka waktu 30 (tiga puluh) hari penyampaian SPOP oleh Wajib Pajak; atau

ii. SPOP disampaikan oleh Wajib Pajak dalam hal SPOP disampaikan karena penundaan atau surat teguran;

(c) menindaklanjuti Peta yang disampaikan oleh Wajib Pajak sebagai dokumen pendukung isian SPOP untuk dilakukan Pengolahan Peta;

(d) dalam hal Wajib Pajak membuat Surat Pernyataan yang ditandatangani oleh Wajib Pajak, wakil Wajib Pajak, atau kuasa dari Wajib Pajak, dan menjelaskan alasan belum dapat dilampirkannya dokumen pendukung isian SPOP, maka kepada Wajib Pajak tersebut dikirimkan Surat Konfirmasi;

(e) Surat Konfirmasi sebagaimana dimaksud dalam huruf (d) disampaikan kepada Wajib Pajak melalui pos, jasa pengiriman, atau cara lain yang ditetapkan oleh Direktur Jenderal Pajak paling lama 14 (empat belas) hari sejak SPOP diterima oleh KPP;

(f) dalam hal Wajib Pajak tidak melampirkan dokumen pendukung isian SPOP setelah disampaikan Surat Konfirmasi sebagaimana dimaksud dalam huruf (d), maka ditindaklanjuti dengan Prosedur Pembuatan Berita Acara Wajib Pajak yang Tidak Melengkapi atau Tidak Menyampaikan Dokumen Pendukung Isian SPOP PBB Sektor Perhutanan Setelah Dikirimkan Surat Konfirmasi oleh KPP; dan

(g) berita acara sebagaimana dimaksud dalam huruf (f), dapat ditindaklanjuti dengan pembuatan analisis risiko usulan Pemeriksaan sesuai dengan ketentuan peraturan perundang-undangan di bidang perpajakan.

(2) Prosedur kerja dan formulir yang digunakan dalam rangka Pengumpulan Peta ditentukan sebagai berikut:

(a) Penyusunan Daftar Ketersediaan Peta Objek Pajak dan Laporan Perkembangan Pengumpulan Peta dan Pengolahan Peta di KPP sebagaimana dimaksud pada angka (1) huruf (b), dibuat dengan menggunakan:

i. prosedur sebagaimana tercantum dalam Lampiran huruf A;

ii. formulir Daftar Ketersediaan Peta Objek Pajak sesuai contoh format sebagaimana tercantum dalam Lampiran huruf B;

iii. Laporan Perkembangan Pengumpulan Peta dan Pengolahan Peta sesuai contoh format sebagaimana tercantum dalam Lampiran huruf C;

(b) Pengumpulan Peta melalui Penyampaian SPOP PBB Sektor Perhutanan di KPP sebagaimana dimaksud pada angka (1) dilakukan sesuai prosedur sebagaimana tercantum dalam Lampiran huruf D;

(c) Surat Konfirmasi sebagaimana dimaksud pada angka (1) huruf (d) dibuat menggunakan formulir sesuai contoh format sebagaimana tercantum dalam Lampiran huruf E;

(d) Berita Acara Wajib Pajak Tidak Melengkapi atau Tidak Menyampaikan Dokumen Pendukung Isian SPOP sebagaimana dimaksud pada angka (1) huruf (f), dibuat dengan menggunakan:

i. prosedur ...

i. prosedur sebagaimana tercantum dalam Lampiran huruf F; dan
ii. formulir sesuai contoh format sebagaimana tercantum dalam Lampiran huruf G,

yang merupakan bagian tidak terpisahkan dari Surat Edaran Direktur Jenderal ini.

b) Pengumpulan Peta melalui kegiatan pengawasan dan/atau Pemeriksaan.
(1) Kepala KPP mengidentifikasi ketersediaan Peta Kerja Wajib Pajak sektor perhutanan yang sedang dilakukan pengawasan dan/atau Pemeriksaan.
(2) Kepala KPP merekapitulasi Peta Kerja dengan menyusun Daftar Ketersediaan Peta Objek dan Laporan Perkembangan Pengumpulan Peta dan Pengolahan Peta, serta mengirimkannya kepada Kepala Kanwil DJP setiap triwulan paling lambat 10 (sepuluh) hari setelah triwulan berakhir.
(3) Kepala KPP meminta Peta kepada Wajib Pajak sektor perhutanan yang sedang dilakukan pengawasan dan/atau Pemeriksaan, dan belum menyampaikan Peta sebagai dokumen pendukung isian SPOP.
(4) Peta yang diperoleh dari Wajib Pajak ditindaklanjuti dengan prosedur Pengolahan Peta, sepanjang Peta tersebut memenuhi kriteria untuk diolah sesuai standar.
(5) Pengumpulan Peta terhadap Wajib Pajak yang sedang dilakukan pengawasan dan/atau Pemeriksaan di KPP tercantum dalam Lampiran huruf H yang merupakan bagian tidak terpisahkan dari Surat Edaran Direktur Jenderal ini.
(6) Contoh format:
(a) Daftar Ketersediaan Peta Objek Pajak tercantum dalam Lampiran huruf B;
(b) Laporan Perkembangan Pengumpulan Peta dan Pengolahan Peta tercantum dalam Lampiran huruf C,

yang merupakan bagian tidak terpisahkan dari Surat Edaran Direktur Jenderal ini.

2) Kanwil DJP
Kepala Kanwil DJP melakukan beberapa hal sebagai berikut:
a) memberikan bimbingan kepada Kepala KPP terkait kegiatan Pengumpulan Peta;
b) melakukan *monitoring* dan evaluasi setiap bulan atas kegiatan Pengumpulan Peta;
c) merekapitulasi Daftar Ketersediaan Peta Objek Pajak dan Laporan Perkembangan Pengumpulan Peta dan Pengolahan Peta yang diterima dari Kepala KPP, serta menyampaikannya kepada Direktur Ekstensifikasi dan Penilaian setiap triwulan, sesuai prosedur sebagaimana tercantum dalam Lampiran huruf I yang merupakan bagian tidak terpisahkan dari Surat Edaran Direktur Jenderal ini;
d) melakukan Pengumpulan Peta terhadap Wajib Pajak sektor perhutanan yang sedang dilakukan Pemeriksaan dan/atau sedang mengajukan keberatan, banding, dan pengurangan sesuai prosedur sebagaimana tercantum dalam Lampiran huruf J yang merupakan bagian tidak terpisahkan dari Surat Edaran Direktur Jenderal ini; dan

e) mengoordinasikan ...

e) mengoordinasikan Pengumpulan Peta dalam hal lokasi Objek Pajak PBB Sektor Perhutanan berada pada lebih dari 1 (satu) wilayah kerja KPP yang masih di dalam 1 (satu) wilayah kerja Kanwil DJP.

3) KPDJP

Direktur Ekstensifikasi dan Penilaian melakukan beberapa hal sebagai berikut:

a) memberikan bimbingan kepada Kepala Kanwil DJP terkait kegiatan Pengumpulan Peta;
b) melakukan *monitoring* dan evaluasi secara periodik atas kegiatan Pengumpulan Peta berdasarkan Daftar Ketersediaan Peta Objek Pajak dan Laporan Perkembangan Pengumpulan Peta dan Pengolahan Peta yang disampaikan oleh Kepala Kanwil DJP;
c) melakukan koordinasi dengan Direktorat Data dan Informasi Perpajakan dan Direktorat Teknologi Informasi dan Komunikasi dalam penyediaan aplikasi Basis Data Spasial PBB untuk mengolah dan menyajikan informasi hasil kegiatan Pengumpulan Peta dan Pengolahan Peta Objek Pajak; dan
d) melakukan koordinasi dengan pihak ILAP dalam rangka penyediaan Peta sektor perhutanan.

4. Pengolahan Peta

Kegiatan Pengolahan Peta dilakukan di unit kerja DJP sebagai berikut:

a. KPP

1) Kepala KPP melakukan beberapa hal sebagai berikut:
   a) mengolah Peta agar sesuai dengan standar yang ditentukan;
   b) mengunggah Peta yang sudah memenuhi standar yang ditentukan pada aplikasi yang telah disediakan oleh DJP;
   c) menyusun Laporan Perkembangan Pengumpulan Peta dan Pengolahan Peta serta mengirimkannya kepada Kepala Kanwil DJP setiap triwulan yang disampaikan paling lambat 10 (sepuluh) hari setelah triwulan berakhir; dan
   d) dapat mengajukan permintaan bantuan penugasan Penilai Pajak ke Kanwil DJP untuk membantu Pengolahan Peta di KPP dalam hal KPP:
      (1) tidak memiliki Penilai Pajak; atau
      (2) Penilai Pajak tidak dapat menyelesaikan seluruh target pemetaan objek pajak dengan mempertimbangkan analisis beban kerja.
2) Standar untuk Pengolahan Peta atas Peta Kerja sebagaimana dimaksud pada angka 1) huruf a) merupakan standar yang telah ditentukan melalui Registrasi Peta berdasarkan sistem referensi koordinat WGS 84 EPSG:4326.
3) Standar Peta sebagaimana dimaksud pada angka 1) huruf a) tercantum dalam Lampiran huruf K yang merupakan bagian tidak terpisahkan dari Surat Edaran Direktur Jenderal ini.
4) Laporan sebagaimana dimaksud pada angka 1) huruf c) dibuat sesuai dengan contoh format sebagaimana tercantum dalam Lampiran huruf C yang merupakan bagian tidak terpisahkan dari Surat Edaran Direktur Jenderal ini.
5) Prosedur Pengolahan Peta di KPP tercantum dalam Lampiran huruf L yang merupakan bagian tidak terpisahkan dari Surat Edaran Direktur Jenderal ini.

b. Kanwil ...

b. Kanwil DJP

Kepala Kanwil DJP melakukan beberapa hal sebagai berikut:

1) melakukan *monitoring* dan evaluasi setiap bulan atas kegiatan Pengolahan Peta yang dilakukan oleh KPP;
2) merekapitulasi Laporan Perkembangan Pengumpulan Peta dan Pengolahan Peta, serta mengirimkannya ke Direktur Ekstensifikasi dan Penilaian setiap triwulan paling lambat 20 (dua puluh) hari setelah triwulan berakhir sesuai dengan contoh format sebagaimana tercantum dalam Lampiran huruf C yang merupakan bagian tidak terpisahkan dari Surat Edaran Direktur Jenderal ini; dan
3) mengoordinasikan Penilai Pajak di Kanwil DJP untuk membantu Pengolahan Peta di KPP berdasarkan permintaan dari Kepala KPP.

c. KPDJP

Direktur Ekstensifikasi dan Penilaian, melakukan beberapa hal sebagai berikut:

1) memberikan bimbingan kepada Kepala Kanwil DJP secara periodik terkait kegiatan Pengolahan Peta;
2) melakukan *monitoring* dan evaluasi secara periodik atas kegiatan Pengolahan Peta;
3) melakukan Pengolahan Peta dari ILAP agar dapat disajikan dalam aplikasi Basis Data Spasial PBB; dan
4) melakukan koordinasi dengan Direktorat Data dan Informasi Perpajakan dan Direktorat Teknologi Informasi dan Komunikasi dalam penyediaan aplikasi Basis Data Spasial PBB untuk mengolah dan menyajikan informasi hasil kegiatan Pengumpulan Peta dan Pengolahan Peta Objek Pajak.

5. Tindak Lanjut atas Kegiatan Pembentukan Basis Data Spasial

Berdasarkan basis Data Spasial yang telah dibentuk melalui kegiatan Pengumpulan Peta dan Pengolahan Peta, baik yang bersumber dari data Wajib Pajak maupun dari data ILAP, dapat dilakukan Analisis Spasial dalam rangka pengujian pelaporan SPOP Wajib Pajak. Kegiatan tersebut dilakukan melalui penyandingan Data Spasial yang bersumber dari Wajib Pajak dengan Data Spasial yang bersumber dari ILAP. Dalam hal terdapat indikasi Wajib Pajak tidak/belum melaporkan sesuai dengan keadaan yang sebenarnya, maka dapat ditindaklanjuti dengan analisis risiko usulan Pemeriksaan.

6. Ketentuan Lain-lain

Dalam hal terdapat penataan organisasi yang menyebabkan perubahan struktur organisasi di lingkungan DJP, maka penunjukan direktorat, bidang, dan seksi yang memiliki tugas dan fungsi pendataan, Pemeriksaan, keberatan, banding, dan pengurangan terkait Pengumpulan Peta dan Pengolahan Peta disesuaikan dengan ketentuan perubahannya.

F. Penutup ...

F. Penutup

Dengan ditetapkannya Surat Edaran Direktur Jenderal ini, petunjuk teknis pembentukan basis Data Spasial Objek Pajak PBB Sektor Perhutanan agar berpedoman pada Surat Edaran Direktur Jenderal ini.

Demikian Surat Edaran Direktur Jenderal ini disampaikan untuk diketahui dan dilaksanakan dengan sebaik-baiknya.

Ditetapkan di Jakarta
pada tanggal 30 Mei 2022

Direktur Jenderal Pajak,

Suryo Utomo

LAMPIRAN
Surat Edaran Direktur Jenderal Pajak
Nomor : SE- 16 /PJ/2022
Tanggal : 30 Mei 2022

A. PROSEDUR PENYUSUNAN DAFTAR KETERSEDIAAN PETA OBJEK PAJAK PBB SEKTOR PERHUTANAN DAN LAPORAN PERKEMBANGAN PENGUMPULAN PETA DAN PENGOLAHAN PETA DI KPP

1. Deskripsi
   Prosedur ini menjelaskan tata cara penyusunan Daftar Ketersediaan Peta Objek Pajak PBB Sektor Perhutanan dan Laporan Perkembangan Pengumpulan Peta dan Pengolahan Peta di KPP.

2. Prosedur Kerja
   a. Kepala Seksi Pengawasan menugasi *Account Representative* untuk menyusun Daftar Ketersediaan Peta Objek Pajak dan Laporan Perkembangan Pengumpulan Peta dan Pengolahan Peta.
   b. *Account Representative* menyusun konsep Daftar Ketersediaan Peta Objek Pajak dan konsep Laporan Perkembangan Pengumpulan Peta dan Pengolahan Peta, serta menyampaikan konsep tersebut kepada Kepala Seksi Pengawasan.
   c. Kepala Seksi Pengawasan meneliti, menyetujui, dan menandatangani konsep Daftar Ketersediaan Peta Objek Pajak dan konsep Laporan Perkembangan Pengumpulan Peta dan Pengolahan Peta, dan mengirimkannya kepada salah satu Kepala Seksi Pengawasan yang ditunjuk oleh Kepala KPP sebagai koordinator kegiatan Pengumpulan Peta dan Pengolahan Peta.
   d. Kepala Seksi Pengawasan yang bertindak sebagai koordinator kegiatan Pengumpulan Peta dan Pengolahan Peta menugasi Pelaksana atau *Account Representative* untuk merekapitulasi daftar dan laporan dari Seksi Pengawasan, dan menyusun konsep Nota Dinas Penyampaian Daftar Ketersediaan Peta Objek Pajak dan Laporan Perkembangan Pengumpulan Peta dan Pengolahan Peta kepada Kepala Kanwil DJP di wilayahnya, beserta daftar dan laporan tersebut.
   e. Pelaksana atau *Account Representative* Seksi Pengawasan yang bertindak sebagai koordinator kegiatan Pengumpulan Peta dan Pengolahan Peta merekapitulasi daftar dan laporan dari Seksi Pengawasan, dan menyusun konsep Nota Dinas Penyampaian Daftar Ketersediaan Peta Objek Pajak dan Laporan Perkembangan Pengumpulan Peta dan Pengolahan Peta kepada Kepala Kanwil DJP di wilayahnya, beserta daftar dan laporan tersebut, serta menyampaikan konsep tersebut kepada Kepala Seksi Pengawasan yang bertindak sebagai koordinator kegiatan Pengumpulan Peta dan Pengolahan Peta.
   f. Kepala Seksi Pengawasan yang bertindak sebagai koordinator kegiatan Pengumpulan Peta dan Pengolahan Peta meneliti, menyetujui, dan memaraf konsep Nota Dinas Penyampaian Daftar Ketersediaan Peta Objek Pajak dan Laporan Perkembangan Pengumpulan Peta dan Pengolahan Peta kepada Kepala Kanwil DJP di wilayahnya, beserta daftar dan laporan tersebut, serta menyampaikan konsep tersebut kepada Kepala KPP.
   g. Kepala KPP meneliti, menyetujui, dan menandatangani konsep Nota Dinas Penyampaian Daftar Ketersediaan Peta Objek Pajak dan Laporan Perkembangan Pengumpulan Peta dan Pengolahan Peta kepada Kepala Kanwil DJP di wilayahnya, beserta daftar dan laporan tersebut.
   h. Proses selesai.

3. Bagan Alir

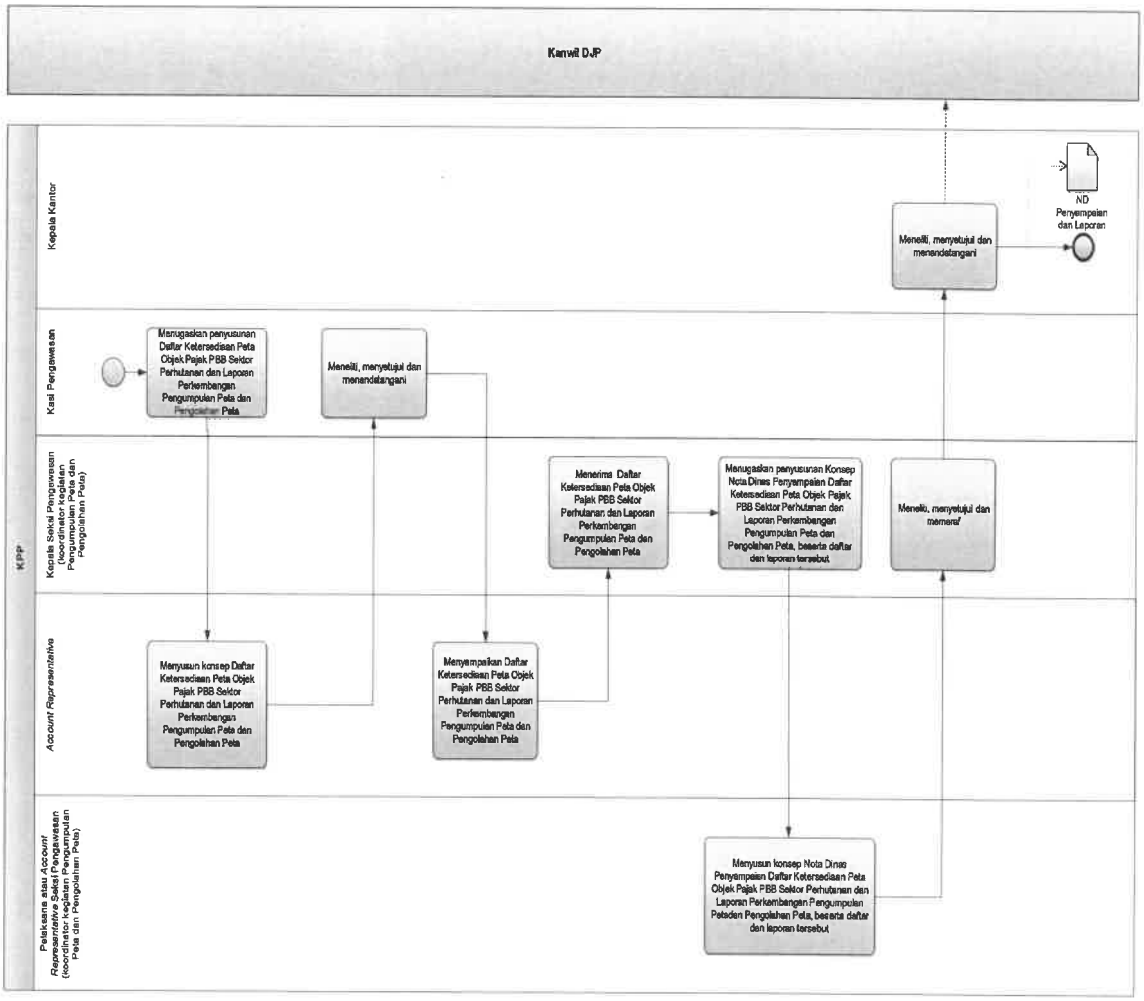
Kanwil DJP
KPP
Kepala Kantor
Kasi Pengawasan
Kepala Seksi Pengawasan (koordinator kegiatan Pengumpulan Peta dan Pengolahan Peta)
Account Representative
Pelaksana atau Account Representative Seksi Pengawasan (koordinator kegiatan Pengumpulan Peta dan Pengolahan Peta)
Menugaskan penyusunan Daftar Ketersediaan Peta Objek Pajak PBB Sektor Perhutanan dan Laporan Perkembangan Pengumpulan Peta dan Pengolahan Peta
Meneliti, menyetujui dan menandatangani
Menerima Daftar Ketersediaan Peta Objek Pajak PBB Sektor Perhutanan dan Laporan Perkembangan Pengumpulan Peta dan Pengolahan Peta
Menugaskan penyusunan Konsep Nota Dinas Penyampaian Daftar Ketersediaan Peta Objek Pajak PBB Sektor Perhutanan dan Laporan Perkembangan Pengumpulan Peta dan Pengolahan Peta, beserta daftar dan laporan tersebut
Meneliti, menyetujui dan memeraf
Menyusun konsep Daftar Ketersediaan Peta Objek Pajak PBB Sektor Perhutanan dan Laporan Perkembangan Pengumpulan Peta dan Pengolahan Peta
Menyampaikan Daftar Ketersediaan Peta Objek Pajak PBB Sektor Perhutanan dan Laporan Perkembangan Pengumpulan Peta dan Pengolahan Peta
Menyusun konsep Nota Dinas Penyampaian Daftar Ketersediaan Peta Objek Pajak PBB Sektor Perhutanan dan Laporan Perkembangan Pengumpulan Peta dan Pengolahan Peta, beserta daftar dan laporan tersebut
Meneliti, menyetujui dan menandatangani
ND Penyampaian dan Laporan

B. FORMAT DAFTAR KETERSEDIAAN PETA OBJEK PAJAK PBB SEKTOR PERHUTANAN

DAFTAR KETERSEDIAAN PETA OBJEK PAJAK PBB SEKTOR PERHUTANAN

NO	NAMA WAJIB PAJAK	NPWP	NOP	KETERSEDIAAN PETA*)		BENTUK PETA*)		BERKOORDINAT*)		KESESUAIAN STANDAR PETA*)		TINDAK LANJUT	KET
				ADA	TIDAK	DIGITAL	LAINNYA	YA	TIDAK	YA	TIDAK		
(1)	(2)	(3)	(4)	(5)	(6)	(7)	(8)	(9)	(10)	(11)	(12)	(13)	(14)
1													
2													
3													
dst													

NB: *) pilih salah satu

....., ... (15)

..... (16)

PETUNJUK PENGISIAN
DAFTAR KETERSEDIAAN PETA OBJEK PAJAK PBB SEKTOR PERHUTANAN

Nomor (1)	:	Diisi dengan nomor urut pengisian.
Nomor (2)	:	Diisi dengan nama Wajib Pajak.
Nomor (3)	:	Diisi dengan Nomor Pokok Wajib Pajak.
Nomor (4)	:	Diisi dengan Nomor Objek Pajak.
Nomor (5)	:	Diisi dengan tanda [✓] jika Peta dari Wajib Pajak tersedia.
Nomor (6)	:	Diisi dengan tanda [✓] jika Peta dari Wajib Pajak tidak tersedia.
Nomor (7)	:	Diisi dengan tanda [✓] jika Peta dari Wajib Pajak berbentuk digital/*softcopy*.
Nomor (8)	:	Diisi dengan tanda [✓] jika Peta dari Wajib Pajak berbentuk selain digital/*hardcopy*.
Nomor (9)	:	Diisi dengan tanda [✓] jika Peta dari Wajib Pajak memiliki koordinat.
Nomor (10)	:	Diisi dengan tanda [✓] jika Peta dari Wajib Pajak tidak memiliki koordinat.
Nomor (11)	:	Diisi dengan tanda [✓] jika Peta dari Wajib Pajak sudah sesuai standar.
Nomor (12)	:	Diisi dengan tanda [✓] jika Peta dari Wajib Pajak tidak sesuai standar.
Nomor (13)	:	Diisi dengan tindak lanjut atas Peta dari Wajib Pajak yang diperoleh (contoh: sudah dikirim Surat Konfirmasi atas Surat Pernyataan Wajib Pajak/sedang dilakukan digitasi/sudah diunggah, dan lain-lain).
Nomor (14)	:	Diisi dengan keterangan lain yang diperlukan (tahun pembuatan peta, nomor Surat Konfirmasi atas Surat Pernyataan Wajib Pajak, tahun pengunggahan, dan lain-lain).
Nomor (15)	:	Diisi dengan tempat dan tanggal penandatangan Daftar Ketersediaan Peta Objek Pajak PBB Sektor Perhutanan.
Nomor (16)	:	Diisi dengan nama dan tanda tangan Kepala Kantor.

C. FORMAT LAPORAN PERKEMBANGAN PENGUMPULAN PETA DAN PENGOLAHAN PETA

LAPORAN PERKEMBANGAN PENGUMPULAN PETA DAN PENGOLAHAN PETA

NO	NAMA WP	NPWP	NOP	PETA DIPEROLEH				PETA TIDAK DIPEROLEH		SURAT KONFIRMASI		KET
				PETA TIDAK DAPAT DIOLAH*)	DALAM PROSES PENGOLAHAN	TELAH DIUNGGAH	SESUAI STANDAR **)	SPOP BELUM KEMBALI	SURAT PERNYA TAAN	RESPON	TIDAK RESPON	
(1)	(2)	(3)	(4)	(5)	(6)	(7)	(8)	(9)	(10)	(11)	(12)	(13)
1												
2												
3												
dst												

....., ... (14)

..... (15)

PETUNJUK PENGISIAN
LAPORAN PERKEMBANGAN PENGUMPULAN PETA DAN PENGOLAHAN PETA

Nomor (1)	:	Diisi dengan nomor urut pengisian.
Nomor (2)	:	Diisi dengan nama Wajib Pajak.
Nomor (3)	:	Diisi dengan Nomor Pokok Wajib Pajak.
Nomor (4)	:	Diisi dengan Nomor Objek Pajak.
Nomor (5)	:	Diisi dengan tanda [✓] jika Peta tidak dapat diolah.
Nomor (6)	:	Diisi dengan tanda [✓] jika Peta masih dalam proses pengolahan.
Nomor (7)	:	Diisi dengan tanda [✓] jika Peta telah diunggah pada aplikasi yang telah disediakan oleh Direktorat Jenderal Pajak.
Nomor (8)	:	Diisi dengan tanda [✓] jika Peta sudah ditampilkan dalam menu *monitoring* pada aplikasi yang telah disediakan oleh Direktorat Jenderal Pajak.
Nomor (9)	:	Diisi dengan tanda [✓] jika SPOP belum dikembalikan oleh Wajib Pajak.
Nomor (10)	:	Diisi dengan tanda [✓] jika Wajib Pajak membuat Surat Pernyataan Belum Dapat Melampirkan Dokumen Pendukung Isian SPOP.
Nomor (11)	:	Diisi dengan tanda [✓] jika Wajib Pajak merespon Surat Konfirmasi atas Surat Penyataan Wajib Pajak.
Nomor (12)	:	Diisi dengan tanda [✓] jika Wajib Pajak tidak merespon Surat Konfirmasi atas Surat Penyataan Wajib Pajak.
Nomor (13)	:	Diisi dengan keterangan Pengumpulan Peta (melalui SPOP/pengawasan/Pemeriksaan) dan keterangan Pengolahan Peta (sedang diolah/sudah diunggah oleh Sdr. A).
Nomor (14)	:	Diisi dengan tempat dan tanggal penandatanganan Laporan Perkembangan Pengumpulan Peta dan Pengolahan Peta.
Nomor (15)	:	Diisi dengan nama dan tanda tangan Kepala Kantor.

NB:

*) Kategori Peta tidak dapat diolah diantaranya Peta tidak berkoordinat, Peta sketsa, dan lain-lain yang tidak bisa dilakukan konversi Peta secara langsung sehingga harus dilakukan pengecekan ke lapangan.

**) Peta dinyatakan sesuai standar jika sudah ditampilkan dalam menu *monitoring* pada aplikasi yang telah disediakan oleh Direktorat Jenderal Pajak.

D. PROSEDUR PENGUMPULAN PETA MELALUI PENYAMPAIAN SPOP PBB SEKTOR PERHUTANAN DI KPP

1. Deskripsi
   Prosedur ini menjelaskan tata cara Pengumpulan Peta yang dilakukan oleh KPP melalui penyampaian SPOP PBB Sektor Perhutanan oleh Wajib Pajak sektor perhutanan.

2. Prosedur Kerja
   a. Kepala Seksi Pengawasan menugasi *Account Representative* untuk mengidentifikasi kelengkapan Dokumen Pendukung Isian SPOP berupa Peta Kerja.
   b. *Account Representative* mengidentifikasi kelengkapan Dokumen Pendukung Isian SPOP berupa Peta Kerja, dalam hal:
      1) Wajib Pajak menyampaikan Peta Kerja, maka ditindaklanjuti dengan menyampaikannya kepada Penilai Pajak untuk dilakukan Pengolahan Peta; atau
      2) Wajib Pajak menyampaikan Surat Pernyataan, maka ditindaklanjuti dengan menyusun konsep Surat Konfirmasi, serta menyampaikan konsep tersebut kepada Kepala Seksi Pengawasan.
   c. Kepala Seksi Pengawasan meneliti, menyetujui, dan memaraf konsep Surat Konfirmasi, serta menyampaikan konsep tersebut kepada Kepala KPP.
   d. Kepala KPP meneliti, menyetujui, dan menandatangani konsep Surat Konfirmasi, serta menyerahkan Surat Konfirmasi tersebut kepada Kepala Seksi Pengawasan.
   e. Kepala Seksi Pengawasan menyerahkan Surat Konfirmasi kepada *Account Representative*.
   f. *Account Representative* menyampaikan Surat Konfirmasi kepada Wajib Pajak.
   g. Atas konfirmasi dari Wajib Pajak:
      1) *Account Representative* melakukan pembaruan terhadap Daftar Ketersediaan Peta Objek Pajak PBB Sektor Perhutanan dalam hal Wajib Pajak menyampaikan dokumen pendukung isian SPOP, serta menyampaikan Daftar Ketersediaan Peta Objek Pajak PBB Sektor Perhutanan yang telah diperbarui beserta Peta yang diperoleh dari Wajib Pajak kepada Pelaksana atau *Account Representative* Seksi Pengawasan yang bertindak sebagai koordinator kegiatan Pengumpulan Peta dan Pengolahan Peta; atau
      2) *Account Representative* menindaklanjuti Wajib Pajak yang tidak melengkapi atau tidak menyampaikan dokumen pendukung isian SPOP sesuai Prosedur Pengumpulan Peta terhadap Wajib Pajak yang Tidak Melengkapi atau Tidak Menyampaikan Dokumen Pendukung Isian SPOP.
   h. Pelaksana atau *Account Representative* Seksi Pengawasan yang bertindak sebagai koordinator kegiatan Pengumpulan Peta dan Pengolahan Peta menyampaikan Peta Kerja yang diterima dari *Account Representative* sebagaimana dimaksud pada huruf g angka 1) kepada Penilai Pajak untuk dilakukan Pengolahan Peta.
   i. Proses selesai.

3. Bagan Alir

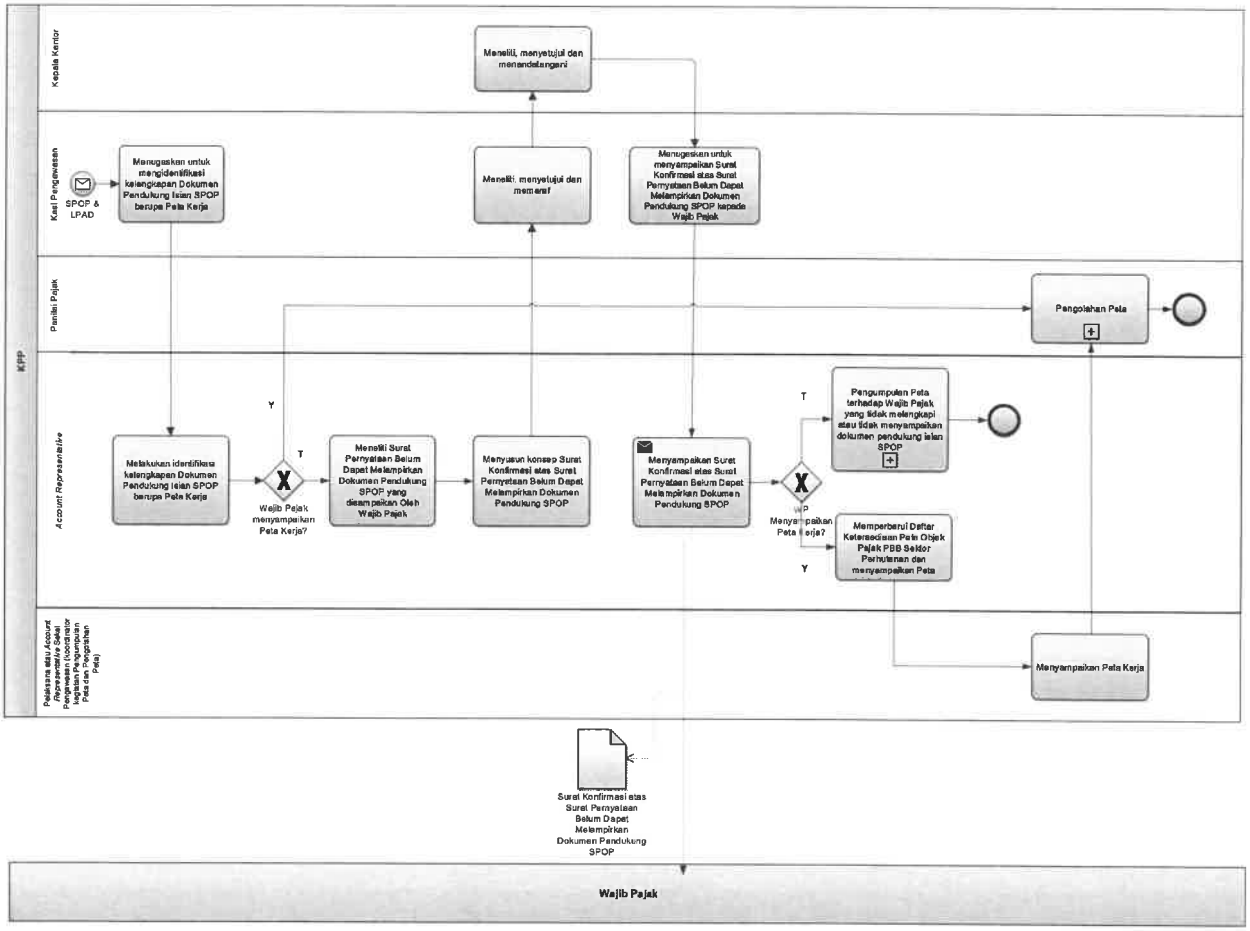
KPP
Kepala Kantor
Meneliti, menyetujui dan menandatangani
Ketua Pengawasan
SPOP & LPAD
Menugaskan untuk mengidentifikasi kelengkapan Dokumen Pendukung Isian SPOP berupa Peta Kerja
Meneliti, menyetujui dan memaraf
Menugaskan untuk menyampaikan Surat Konfirmasi atas Surat Pernyataan Belum Dapat Melampirkan Dokumen Pendukung SPOP kepada Wajib Pajak
Pemeriksa Pajak
Pengolahan Peta
Account Representative
Melakukan identifikasi kelengkapan Dokumen Pendukung Isian SPOP berupa Peta Kerja
Y
T
Wajib Pajak menyampaikan Peta Kerja?
Meneliti Surat Pernyataan Belum Dapat Melampirkan Dokumen Pendukung SPOP yang disampaikan Oleh Wajib Pajak
Menyusun konsep Surat Konfirmasi atas Surat Pernyataan Belum Dapat Melampirkan Dokumen Pendukung SPOP
Menyampaikan Surat Konfirmasi atas Surat Pernyataan Belum Dapat Melampirkan Dokumen Pendukung SPOP
T
Pengumpulan Peta terhadap Wajib Pajak yang tidak melengkapi atau tidak menyampaikan dokumen pendukung isian SPOP
Wajib Pajak Menyampaikan Peta Kerja?
Y
Memperbarui Daftar Ketersediaan Peta Objek Pajak PBB Sektor Perkebunan dan menyampaikan Peta
Pelaksana atau Account Representative Selaku Pengawasan (Koordinator Kegiatan Pengumpulan Data Pengolahan Peta)
Menyampaikan Peta Kerja
Surat Konfirmasi atas Surat Pernyataan Belum Dapat Melampirkan Dokumen Pendukung SPOP
Wajib Pajak

E. FORMAT SURAT KONFIRMASI ATAS SURAT PERNYATAAN BELUM DAPAT MELAMPIRKAN DOKUMEN PENDUKUNG SPOP

KEMENTERIAN KEUANGAN REPUBLIK INDONESIA
DIREKTORAT JENDERAL PAJAK
..... (1)

Nomor : S..... (2) ..... (3)
Sifat : Sangat Segera
Hal : Konfirmasi atas Surat Pernyataan Belum Dapat Melampirkan Dokumen Pendukung Surat Pemberitahuan Objek Pajak (SPOP)

Yth ..... (4)
NPWP ..... (5)
NOP ..... (6)
Jl ..... (7)

Sesuai dengan Surat Pernyataan Belum Dapat Melampirkan Dokumen Pendukung SPOP yang Saudara sampaikan, dengan ini kami informasikan beberapa hal sebagai berikut:

1. Berdasarkan ketentuan:
   a. Pasal 9 ayat (2) Undang-Undang Nomor 12 Tahun 1985 tentang Pajak Bumi dan Bangunan sebagaimana telah diubah dengan Undang-Undang Nomor 12 Tahun 1994 diatur bahwa SPOP harus diisi dengan **jelas, benar, dan lengkap** serta ditandatangani dan disampaikan kepada Direktorat Jenderal Pajak yang wilayah kerjanya meliputi letak objek pajak, paling lambat 30 (tiga puluh) hari setelah tanggal diterimanya SPOP oleh Wajib Pajak.
   b. Pasal 14 Peraturan Menteri Keuangan Nomor 48/PMK.03/2021 tentang Tata Cara Pendaftaran, Pelaporan, dan Pendataan Objek Pajak Pajak Bumi dan Bangunan dijelaskan bahwa SPOP yang disampaikan oleh Wajib Pajak harus jelas, benar, lengkap, dan ditandatangani **serta dilampiri dengan dokumen pendukung isian SPOP**.
   c. Huruf E Formulir SPOP sesuai dengan Lampiran Peraturan Direktur Jenderal Pajak Nomor PER-23/PJ/2021 tentang Surat Pemberitahuan Objek Pajak Pajak Bumi dan Bangunan, Wajib Pajak Pajak Bumi dan Bangunan Sektor Perhutanan harus melampirkan beberapa dokumen sebagai berikut:
      (1) Formulir L-2A;
      (2) Formulir L-2B;
      (3) Formulir L-7;
      (4) Dokumen IUPHHK-HA/ IUPHHK-HTI/ IUPHHK-RE/ IUPHHBK-HA/ IUPHHBK-HT/ Penugasan;
      (5) Rencana Kerja Usaha;
      (6) Rencana Kerja Tahunan;
      (7) Peta Kerja; dan
      (8) Surat Pernyataan.

2. Berdasarkan hasil penelitian, Saudara belum melampirkan dokumen pendukung SPOP berupa ..... (8).
   Sehubungan dengan hal tersebut, agar Saudara menyampaikan kepada kami dokumen dimaksud paling lama 30 (tiga puluh) hari sejak: ..... (9)
   Berakhirnya jangka waktu 30 (tiga puluh) hari setelah tanggal diterimanya SPOP oleh Wajib Pajak;
   SPOP disampaikan oleh Wajib Pajak melalui penundaan penyampaian SPOP;
   SPOP disampaikan oleh Wajib Pajak setelah diterbitkannya surat teguran penyampaian SPOP.

3. Apabila Saudara memerlukan penjelasan/informasi lebih lanjut dapat menghubungi:
   Nama : ..... (10)
   Jabatan : *Account Representative*
   Telepon : ..... (11)

Demikian disampaikan, atas perhatian dan kerja samanya yang baik diucapkan terima kasih.

Kepala Kantor,

..... (12)

PETUNJUK PENGISIAN
SURAT KONFIRMASI ATAS SURAT PERNYATAAN BELUM DAPAT MENYAMPAIKAN DOKUMEN PENDUKUNG SPOP

Nomor (1)	:	Diisi dengan nama kantor dan alamat kantor sebagai kepala surat.
Nomor (2)	:	Diisi dengan nomor surat yang ditujukan kepada Wajib Pajak.
Nomor (3)	:	Diisi dengan tanggal surat kepada Wajib Pajak.
Nomor (4)	:	Diisi dengan nama Wajib Pajak.
Nomor (5)	:	Diisi dengan Nomor Pokok Wajib Pajak.
Nomor (6)	:	Diisi dengan Nomor Objek Pajak.
Nomor (7)	:	Diisi dengan alamat Wajib Pajak.
Nomor (8)	:	Diisi dengan dokumen pendukung SPOP yang belum dilampirkan oleh Wajib Pajak.
Nomor (9)	:	Diisi dengan memberikan tanda silang [X] pada kotak sesuai dengan pilihan Wajib Pajak yang disampaikan pada Surat Pernyataan Belum Dapat Melampirkan Dokumen Pendukung SPOP.
Nomor (10)	:	Diisi dengan nama *Account Representative*.
Nomor (11)	:	Diisi dengan nomor telepon kantor dan nomor *extension.*
Nomor (12)	:	Diisi dengan tanda tangan dan nama Kepala Kantor yang menandatangani surat.

F. PROSEDUR PEMBUATAN BERITA ACARA WAJIB PAJAK TIDAK MELENGKAPI ATAU TIDAK MENYAMPAIKAN DOKUMEN PENDUKUNG ISIAN SPOP SETELAH DIKIRIMKAN SURAT KONFIRMASI OLEH KPP

1. Deskripsi
   Prosedur ini menjelaskan tata cara pembuatan Berita Acara Wajib Pajak Tidak Melengkapi atau Tidak Menyampaikan Dokumen Pendukung Isian SPOP setelah dikirimkan Surat Konfirmasi oleh KPP.

2. Prosedur Kerja
   a. *Account Representative* menyusun konsep Berita Acara Wajib Pajak Tidak Melengkapi atau Tidak Menyampaikan Dokumen Pendukung Isian SPOP dan menyampaikannya kepada Kepala Seksi Pengawasan. Konsep Berita Acara Wajib Pajak Tidak Melengkapi atau Tidak Menyampaikan Dokumen Pendukung Isian SPOP dibuat paling lama 7 (tujuh) hari setelah jangka waktu yang ditentukan pada Surat Konfirmasi terlampaui.
   b. Kepala Seksi Pengawasan meneliti, menyetujui, dan menandatangani konsep Berita Acara Wajib Pajak Tidak Melengkapi atau Tidak Menyampaikan Dokumen Pendukung Isian SPOP dan selanjutnya menugasi *Account Representative* untuk menyusun konsep Laporan Analisis Risiko Usulan Pemeriksaan.
   c. *Account Representative* menyusun konsep Laporan Analisis Risiko Usulan Pemeriksaan dan menyampaikan kepada Kepala Seksi Pengawasan.
   d. Kepala Seksi Pengawasan meneliti, menyetujui, dan menandatangani Laporan Analisis Risiko Usulan Pemeriksaan, serta menugasi *Account Representative* untuk menyampaikan laporan tersebut kepada Kepala Seksi Pemeriksaan, Penilaian dan Penagihan.
   e. *Account Representative* menyampaikan Laporan Analisis Risiko Usulan Pemeriksaan kepada Kepala Seksi Pemeriksaan, Penilaian dan Penagihan.
   f. Kepala Seksi Pemeriksaan, Penilaian dan Penagihan dapat menindaklanjuti Laporan Analisis Risiko Usulan Pemeriksaan sesuai dengan prosedur Pemeriksaan.
   g. Proses selesai.

3. Bagan alir

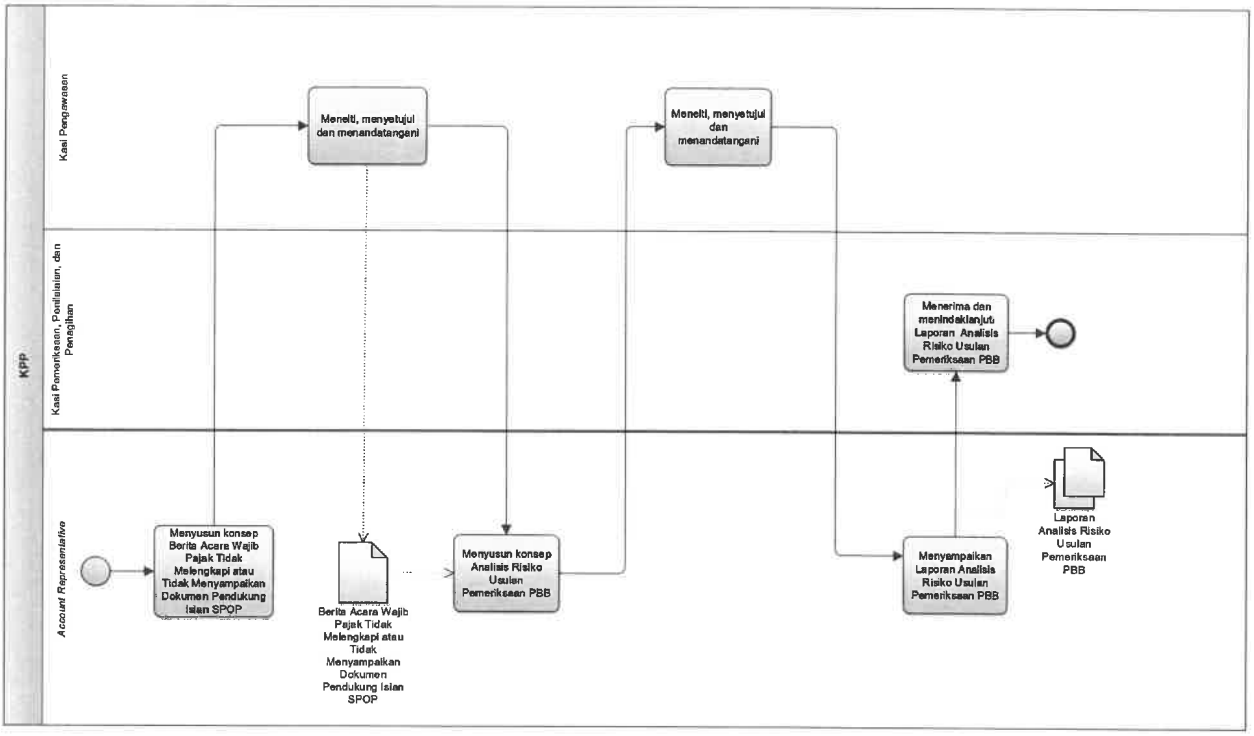
KPP
Account Representative
Kasi Pemeriksaan, Penilaian, dan Penagihan
Kasi Pengawasan
Menyusun konsep Berita Acara Wajib Pajak Tidak Melengkapi atau Tidak Menyampaikan Dokumen Pendukung Isian SPOP
Berita Acara Wajib Pajak Tidak Melengkapi atau Tidak Menyampaikan Dokumen Pendukung Isian SPOP
Meneliti, menyetujui dan menandatangani
Menyusun konsep Analisis Risiko Usulan Pemeriksaan PBB
Meneliti, menyetujui dan menandatangani
Menyampaikan Laporan Analisis Risiko Usulan Pemeriksaan PBB
Laporan Analisis Risiko Usulan Pemeriksaan PBB
Menerima dan menindaklanjuti Laporan Analisis Risiko Usulan Pemeriksaan PBB

G. FORMAT BERITA ACARA WAJIB PAJAK TIDAK MELENGKAPI ATAU TIDAK MENYAMPAIKAN DOKUMEN PENDUKUNG ISIAN SURAT PEMBERITAHUAN OBJEK PAJAK (SPOP)

KEMENTERIAN KEUANGAN REPUBLIK INDONESIA
DIREKTORAT JENDERAL PAJAK
..... (1)

Berita Acara Wajib Pajak Tidak Melengkapi atau Tidak Menyampaikan Dokumen Pendukung Isian Surat Pemberitahuan Objek Pajak (SPOP)

Pada hari ini ..... tanggal ..... bulan ..... tahun ..... (2) berdasarkan:

a. identifikasi kelengkapan dokumen pendukung isian SPOP; dan

b. Surat Pernyataan Belum Dapat Melampirkan Dokumen Pendukung SPOP,

yang disampaikan oleh Wajib Pajak pada tanggal ..... (3), kami *Account Representative* dari Direktorat Jenderal Pajak:

Nama : ..... (4)
NIP : ..... (5)
Pangkat/Golongan : ..... (6)

telah menyampaikan Surat Konfirmasi atas Surat Pernyataan Belum Dapat Melampirkan Dokumen Pendukung SPOP melalui Surat nomor:.....(7) atas:

Nama : ..... (8)
NPWP : ..... (9)
NOP : ..... (10)
Alamat objek pajak : ..... (11)
Alasan : ..... (12)

dengan hasil bahwa Wajib Pajak tidak menyampaikan dokumen pendukung isian SPOP sesuai batas waktu yang telah ditentukan.

Demikian Berita Acara ini dibuat dengan sebenar-benarnya dan akan ditindaklanjuti sesuai ketentuan peraturan perundang-undangan perpajakan.

Account Representative

..... (13)

Mengetahui,
Kepala Seksi Pengawasan... (14)

..... (15)

PETUNJUK PENGISIAN
BERITA ACARA WAJIB PAJAK TIDAK MELENGKAPI ATAU TIDAK MENYAMPAIKAN DATA PENDUKUNG ISIAN SURAT PEMBERITAHUAN OBJEK PAJAK (SPOP)

Nomor (1)	:	Diisi dengan nama kantor dan alamat kantor sebagai kepala surat.
Nomor (2)	:	Diisi dengan hari, tanggal, bulan, dan tahun ditandatangani Berita Acara Tidak Melengkapi atau Tidak Menyampaikan Data Pendukung Isian Surat Pemberitahuan Objek Pajak (SPOP).
Nomor (3)	:	Diisi dengan tanggal penyampaian Surat Pernyataan Belum Dapat Melampirkan Dokumen Pendukung SPOP oleh Wajib Pajak.
Nomor (4)	:	Diisi dengan nama *Account Representative*.
Nomor (5)	:	Diisi dengan NIP *Account Representative*.
Nomor (6)	:	Diisi dengan pangkat/golongan *Account Representative*.
Nomor (7)	:	Diisi dengan Nomor Surat Konfirmasi atas Surat Pernyataan Belum Dapat Melampirkan Dokumen Pendukung SPOP.
Nomor (8)	:	Diisi dengan nama Wajib Pajak.
Nomor (9)	:	Diisi dengan Nomor Pokok Wajib Pajak.
Nomor (10)	:	Diisi dengan Nomor Objek Pajak.
Nomor (11)	:	Diisi dengan alamat objek pajak.
Nomor (12)	:	Diisi dengan alasan sesuai Surat Pernyataan Belum Dapat Melampirkan Dokumen Pendukung SPOP dari Wajib Pajak.
Nomor (13)	:	Diisi dengan nama dan tanda tangan *Account Representative*.
Nomor (14)	:	Diisi dengan nama Seksi Pengawasan dari *Account Representative* yang bersangkutan.
Nomor (15)	:	Diisi dengan nama dan tanda tangan Kepala Seksi Pengawasan

H. PROSEDUR PENGUMPULAN PETA TERHADAP WAJIB PAJAK YANG SEDANG DILAKUKAN PENGAWASAN DAN/ATAU PEMERIKSAAN DI KPP

1. Deskripsi
   Prosedur ini menjelaskan tata cara Pengumpulan Peta terhadap Wajib Pajak yang sedang dilakukan pengawasan dan/atau Pemeriksaan di KPP.

2. Prosedur Kerja
   a. Kepala Seksi Pengawasan menugasi *Account Representative* untuk menyusun daftar Wajib Pajak sektor perhutanan di wilayahnya yang sedang dilakukan pengawasan untuk disampaikan kepada Kepala Seksi Pengawasan yang bertindak sebagai koordinator kegiatan Pengumpulan Peta dan Pengolahan Peta.
   b. *Account Representative* menyusun konsep daftar Wajib Pajak sektor perhutanan di wilayahnya yang sedang dilakukan pengawasan untuk disampaikan kepada Kepala Seksi Pengawasan yang bertindak sebagai koordinator kegiatan Pengumpulan Peta dan Pengolahan Peta.
   c. Kepala Seksi Pengawasan meneliti, menyetujui, dan menandatangani konsep daftar Wajib Pajak sektor perhutanan di wilayahnya yang sedang dilakukan pengawasan, dan mengirimkannya kepada Kepala Seksi Pengawasan yang bertindak sebagai koordinator kegiatan Pengumpulan Peta dan Pengolahan Peta.
   d. Kepala Seksi Pengawasan yang bertindak sebagai koordinator kegiatan Pengumpulan Peta dan Pengolahan Peta menugasi Pelaksana atau *Account Representative* Seksi Pengawasan yang bertindak sebagai koordinator kegiatan Pengumpulan Peta dan Pengolahan Peta untuk menyusun daftar Wajib Pajak sektor perhutanan yang sedang dilakukan pengawasan dan/atau Pemeriksaan.
   e. Pelaksana atau *Account Representative* Seksi Pengawasan yang bertindak sebagai koordinator kegiatan Pengumpulan Peta dan Pengolahan Peta menyusun daftar Wajib Pajak sektor perhutanan yang sedang dilakukan pengawasan dan/atau Pemeriksaan.
   f. Kepala Seksi Pemeriksaan, Penilaian dan Penagihan menugasi Pelaksana Seksi Pemeriksaan, Penilaian dan Penagihan untuk mengidentifikasi dan menyusun daftar Wajib Pajak sektor perhutanan yang sedang dilakukan Pemeriksaan untuk disampaikan kepada Kepala Seksi Pengawasan yang bertindak sebagai koordinator kegiatan Pengumpulan Peta dan Pengolahan Peta.
   g. Pelaksana Seksi Pemeriksaan, Penilaian dan Penagihan menyampaikan daftar Wajib Pajak sektor perhutanan yang sedang dilakukan Pemeriksaan kepada Kepala Seksi Pengawasan yang bertindak sebagai koordinator kegiatan Pengumpulan Peta dan Pengolahan Peta.
   h. Kepala Seksi Pengawasan yang bertindak sebagai koordinator kegiatan Pengumpulan Peta dan Pengolahan Peta menugasi Pelaksana atau *Account Representative* Seksi Pengawasan yang bertindak sebagai koordinator kegiatan Pengumpulan Peta dan Pengolahan Peta untuk melakukan identifikasi ketersediaan Peta Kerja atas daftar Wajib Pajak sektor perhutanan yang sedang dilakukan pengawasan dan/atau Pemeriksaan.
   i. Pelaksana atau *Account Representative* Seksi Pengawasan yang bertindak sebagai koordinator kegiatan Pengumpulan Peta dan Pengolahan Peta melakukan identifikasi ketersediaan Peta Kerja atas daftar Wajib Pajak sektor perhutanan yang sedang dilakukan pengawasan dan/atau Pemeriksaan, dalam hal:
      1) Peta Kerja tersedia, maka Pelaksana atau *Account Representative* Seksi Pengawasan yang bertindak sebagai koordinator kegiatan Pengumpulan Peta dan

Pengolahan Peta memberikan konfirmasi kepada *Account Representative* yang mengawasi Wajib Pajak tersebut serta Pelaksana Seksi Pemeriksaan, Penilaian dan Penagihan bahwa Peta Kerja telah tersedia; atau

2) Peta Kerja tidak tersedia, maka:
   a) *Account Representative* yang mengawasi Wajib Pajak tersebut melaksanakan prosedur permintaan Peta melalui tata cara permintaan penjelasan atas data dan/atau keterangan; dan/atau
   b) Tim Pemeriksa melaksanakan prosedur permintaan Peta melalui tata cara Pemeriksaan atas Wajib Pajak tersebut.

j. *Account Representative* yang mengawasi Wajib Pajak tersebut dan Tim Pemeriksa menyampaikan Peta Kerja kepada Penilai Pajak.
k. Penilai Pajak selanjutnya mengolah Peta Kerja.
l. Proses selesai.

3. Bagan alir

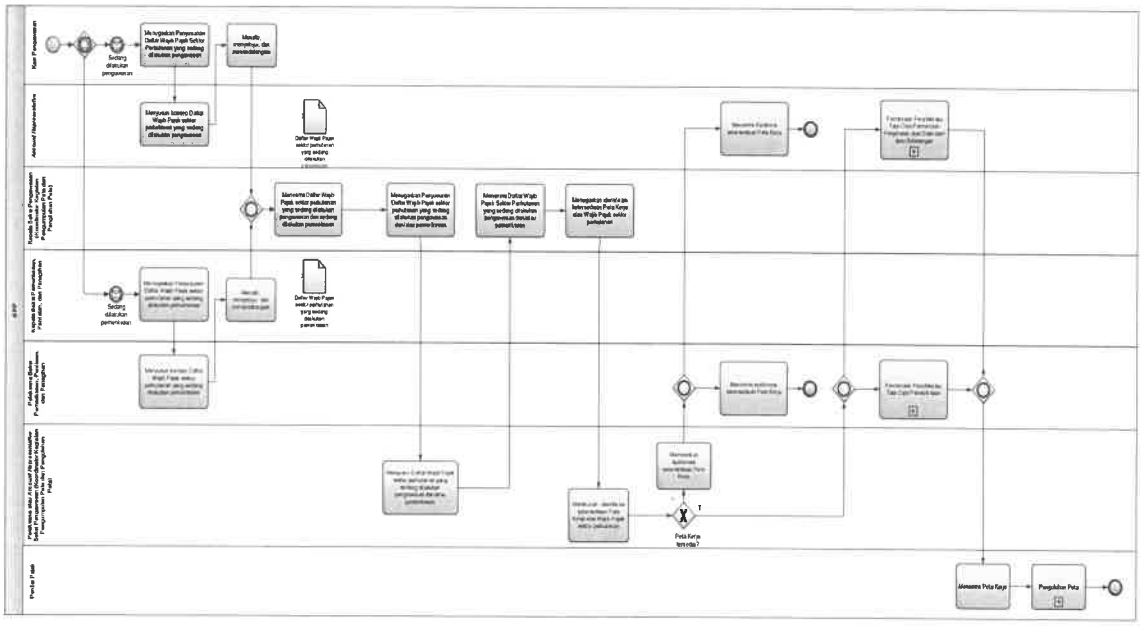

I. PROSEDUR PENGUMPULAN PETA BERDASARKAN DAFTAR KETERSEDIAAN PETA OBJEK PAJAK SEKTOR PERHUTANAN DAN LAPORAN PERKEMBANGAN PENGUMPULAN PETA DAN PENGOLAHAN PETA DI KANWIL DJP

1. Deskripsi
   Prosedur ini menjelaskan tata cara Pengumpulan Peta di Kanwil DJP berdasarkan Daftar Ketersediaan Peta Objek Pajak PBB Sektor Perhutanan dan Laporan Perkembangan Pengumpulan Peta dan Pengolahan Peta yang diterima dari Kepala KPP.

2. Prosedur Kerja
   a. Kepala Kanwil DJP menugasi Kepala Bidang Pendaftaran, Ekstensifikasi, dan Penilaian (PEP) untuk merekapitulasi Daftar Ketersediaan Peta Objek PBB Pajak Sektor Perhutanan dan Laporan Perkembangan Pengumpulan Peta dan Pengolahan Peta untuk disampaikan kepada Direktur Ekstensifikasi dan Penilaian.
   b. Kepala Bidang PEP menugasi Kepala Seksi Bimbingan Pendataan, Penilaian, dan Pengenaan (P3) untuk merekapitulasi Daftar Ketersediaan Peta Objek Pajak PBB Sektor Perhutanan dan Laporan Perkembangan Pengumpulan Peta dan Pengolahan Peta berdasarkan daftar dan laporan yang disampaikan oleh KPP.
   c. Kepala Seksi Bimbingan P3 menugasi Pelaksana Seksi Bimbingan P3 untuk merekapitulasi Daftar Ketersediaan Peta Objek Pajak PBB Sektor Perhutanan dan Laporan Perkembangan Pengumpulan Peta dan Pengolahan Peta berdasarkan daftar dan laporan yang disampaikan oleh KPP.
   d. Pelaksana Seksi Bimbingan P3 menyusun konsep Nota Dinas Penyampaian Daftar Ketersediaan Peta Objek Pajak PBB Sektor Perhutanan dan Laporan Perkembangan Pengumpulan Peta dan Pengolahan Peta dari Kepala Kanwil DJP kepada Direktur Ekstensifikasi dan Penilaian, beserta daftar dan laporan tersebut, serta menyerahkan konsep nota dinas tersebut kepada Kepala Seksi Bimbingan P3.
   e. Kepala Seksi Bimbingan P3 meneliti dan menyetujui konsep Nota Dinas Penyampaian Daftar Ketersediaan Peta Objek Pajak PBB Sektor Perhutanan dan Laporan Perkembangan Pengumpulan Peta dan Pengolahan Peta dari Kepala Kanwil DJP kepada Direktur Ekstensifikasi dan Penilaian, beserta daftar dan laporan tersebut, serta menyampaikan konsep nota dinas tersebut kepada Kepala Bidang PEP.
   f. Kepala Bidang PEP meneliti dan menyetujui konsep Nota Dinas Penyampaian Daftar Ketersediaan Peta Objek Pajak PBB Sektor Perhutanan dan Laporan Perkembangan Pengumpulan Peta dan Pengolahan Peta dari Kepala Kanwil DJP kepada Direktur Ekstensifikasi dan Penilaian, beserta daftar dan laporan tersebut, serta menyampaikan nota dinas tersebut kepada Kepala Kanwil DJP.
   g. Kepala Kanwil DJP meneliti, menyetujui, dan menandatangani Nota Dinas Penyampaian Daftar Ketersediaan Peta Objek Pajak PBB Sektor Perhutanan dan Laporan Perkembangan Pengumpulan Peta dan Pengolahan Peta dari Kepala Kanwil DJP kepada Direktur Ekstensifikasi dan Penilaian, beserta daftar dan laporan tersebut.
   h. Proses selesai.

3. Bagan Alir

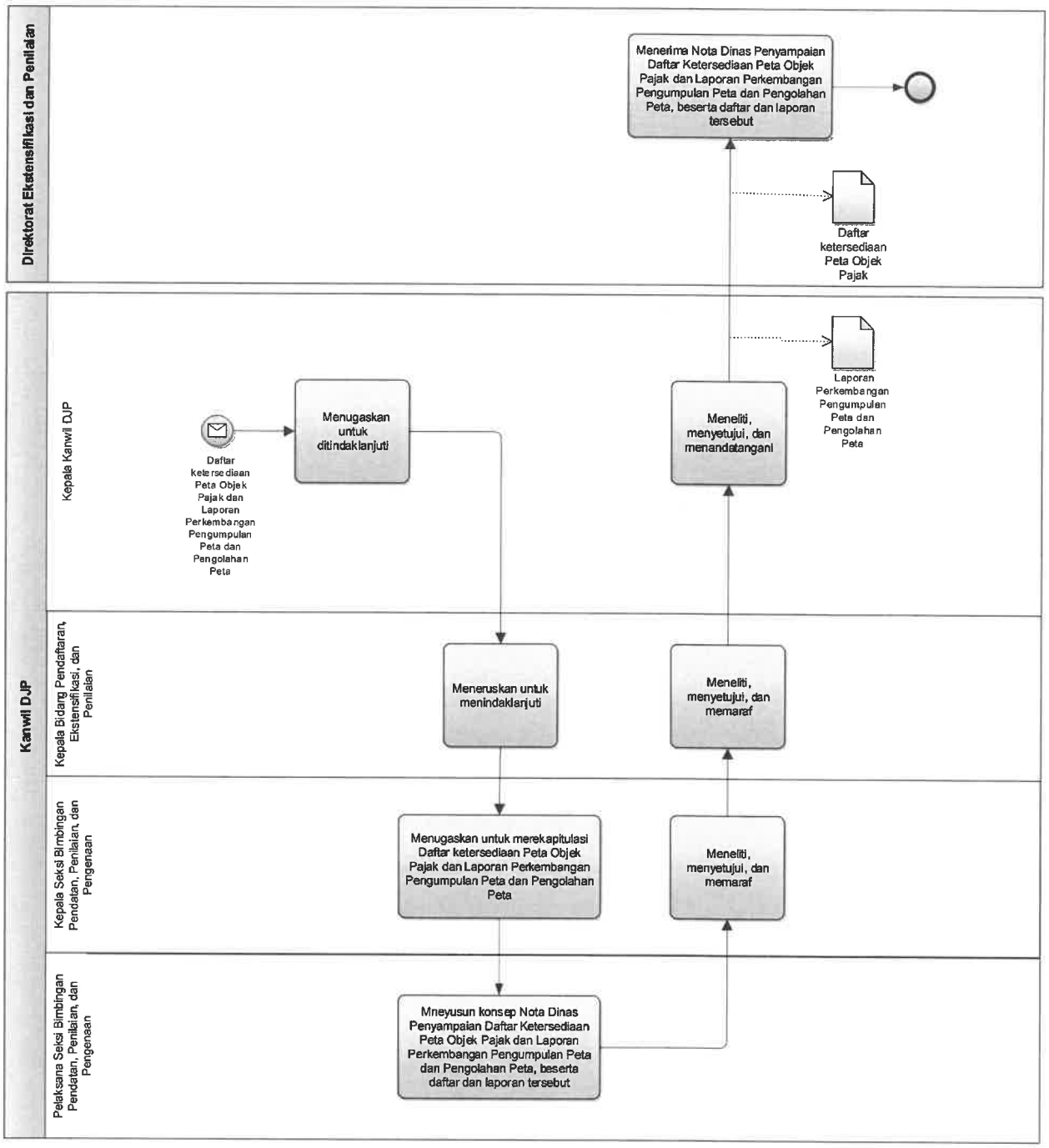
Direktorat Ekstensifikasi dan Penilaian
Kanwil DJP
Kepala Kanwil DJP
Kepala Bidang Pendaftaran, Ekstensifikasi, dan Penilaian
Kepala Seksi Bimbingan Pendatan, Penilaian, dan Pengenaan
Pelaksana Seksi Bimbingan Pendatan, Penilaian, dan Pengenaan
Daftar ketersediaan Peta Objek Pajak dan Laporan Perkembangan Pengumpulan Peta dan Pengolahan Peta
Menugaskan untuk ditindaklanjuti
Meneruskan untuk menindaklanjuti
Menugaskan untuk merekapitulasi Daftar ketersediaan Peta Objek Pajak dan Laporan Perkembangan Pengumpulan Peta dan Pengolahan Peta
Mneyusun konsep Nota Dinas Penyampaian Daftar Ketersediaan Peta Objek Pajak dan Laporan Perkembangan Pengumpulan Peta dan Pengolahan Peta, beserta daftar dan laporan tersebut
Meneliti, menyetujui, dan memaraf
Meneliti, menyetujui, dan memaraf
Meneliti, menyetujui, dan menandatangani
Laporan Perkembangan Pengumpulan Peta dan Pengolahan Peta
Menerima Nota Dinas Penyampaian Daftar Ketersediaan Peta Objek Pajak dan Laporan Perkembangan Pengumpulan Peta dan Pengolahan Peta, beserta daftar dan laporan tersebut
Daftar ketersediaan Peta Objek Pajak

J. PROSEDUR PENGUMPULAN PETA TERHADAP WAJIB PAJAK SEKTOR PERHUTANAN YANG SEDANG DILAKUKAN PEMERIKSAAN DAN/ATAU SEDANG MENGAJUKAN KEBERATAN, BANDING, DAN PENGURANGAN DI KANWIL DJP

1. Deskripsi

   Prosedur ini menjelaskan tata cara Pengumpulan Peta terhadap Wajib Pajak sektor perhutanan yang sedang dilakukan Pemeriksaan dan/atau mengajukan keberatan, banding, dan pengurangan di Kanwil DJP.

2. Prosedur Kerja

   a. Kepala Bidang Pendaftaran, Ekstensifikasi dan Penilaian (PEP) menyusun daftar Wajib Pajak sektor perhutanan yang belum menyampaikan Peta Kerja berdasarkan Laporan Perkembangan Pengumpulan Peta dan Pengolahan Peta dari KPP dan selanjutnya menyampaikan daftar tersebut kepada Kepala Bidang Pemeriksaan, Penagihan, Intelijen, dan Penyidikan (P2IP) dan Kepala Bidang Keberatan, Banding, dan Pengurangan (KBP).

   b. Kepala Bidang P2IP melakukan beberapa hal sebagai berikut:
      1) menyandingkan daftar Wajib Pajak sektor perhutanan yang belum menyampaikan Peta Kerja dengan Wajib Pajak sektor perhutanan yang sedang dilakukan Pemeriksaan;
      2) menindaklanjuti Wajib Pajak sektor perhutanan yang sedang dilakukan Pemeriksaan namun belum menyampaikan Peta Kerja untuk dimintai Peta Kerja sesuai Prosedur Peminjaman Dokumen Dalam Rangka Pemeriksaan; dan
      3) menyampaikan Peta Kerja yang diperoleh melalui Prosedur Peminjaman Dokumen Dalam Rangka Pemeriksaan kepada Kepala Bidang PEP.

   c. Kepala Bidang KBP melakukan beberapa hal sebagai berikut:
      1) menyandingkan daftar Wajib Pajak sektor perhutanan yang belum menyampaikan Peta Kerja dengan Wajib Pajak sektor perhutanan yang sedang mengajukan keberatan, banding, dan pengurangan;
      2) menindaklanjuti Wajib Pajak sektor perhutanan yang sedang mengajukan keberatan, banding, dan pengurangan, namun belum menyampaikan Peta Kerja untuk dimintai Peta Kerja sesuai Prosedur Peminjaman Dokumen Dalam Rangka Penyelesaian Keberatan, Banding, dan Pengurangan; dan
      3) menyampaikan Peta Kerja yang diperoleh melalui Prosedur Peminjaman Dokumen Dalam Rangka Penyelesaian Keberatan, Banding, dan Pengurangan kepada Kepala Bidang PEP.

   d. Kepala Bidang PEP menyampaikan Peta Kerja yang diperoleh melalui prosedur Pemeriksaan dan/atau pengajuan keberatan, banding, dan pengurangan, kepada Kepala KPP.

   e. Kepala KPP menerima Peta Kerja.

   f. Proses selesai.

3. Bagan alir

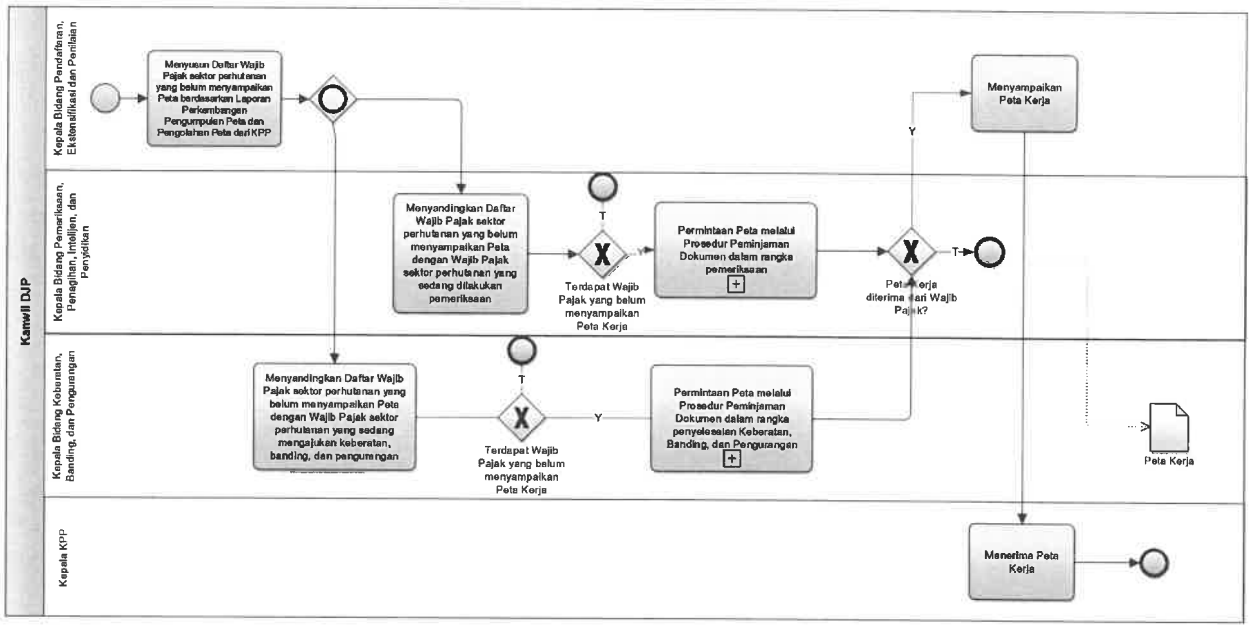
Kanwil DJP
Kepala Bidang Pendaftaran, Ekstensifikasi dan Penilaian
Kepala Bidang Pemeriksaan, Penagihan, Intelijen, dan Penyidikan
Kepala Bidang Keberatan, Banding, dan Pengurangan
Kepala KPP
Menyusun Daftar Wajib Pajak sektor perhutanan yang belum menyampaikan Peta berdasarkan Laporan Perkembangan Pengumpulan Peta dan Pengolahan Peta dari KPP
Menyandingkan Daftar Wajib Pajak sektor perhutanan yang belum menyampaikan Peta dengan Wajib Pajak sektor perhutanan yang sedang dilakukan pemeriksaan
T
Terdapat Wajib Pajak yang belum menyampaikan Peta Kerja
Permintaan Peta melalui Prosedur Peminjaman Dokumen dalam rangka pemeriksaan
Peta Kerja diterima dari Wajib Pajak?
T
Y
Menyampaikan Peta Kerja
Menyandingkan Daftar Wajib Pajak sektor perhutanan yang belum menyampaikan Peta dengan Wajib Pajak sektor perhutanan yang sedang mengajukan keberatan, banding, dan pengurangan
T
Terdapat Wajib Pajak yang belum menyampaikan Peta Kerja
Y
Permintaan Peta melalui Prosedur Peminjaman Dokumen dalam rangka penyelesaian Keberatan, Banding, dan Pengurangan
Peta Kerja
Menerima Peta Kerja

K. STANDAR DAN CONTOH VISUALISASI PETA OBJEK PAJAK PBB SEKTOR PERHUTANAN

1. Standar Peta yang digunakan dalam rangka pembentukan basis data spasial Objek Pajak PBB Sektor Perhutanan terdiri atas:
   a. Hutan Alam

No	Jenis *Layer*	Atribut *Layer*	*Type*	*Length*	Keterangan Pengisian
1	*Layer* Izin	id_izin	*integer*	10	Tidak diisi karena *auto numbering*
		nm_pmg_izn	*text*	64	Diisi nama pemegang izin
	Contoh: 123_IZN	no_izin	*text*	64	Diisi nomor izin
	(Disediakan oleh KPDJP)	tgl_izin	*text*	10	Diisi tanggal izin dengan format dd/mm/yyyy
	Bentuk: Poligon	kd_jns_izn	*integer*	1	Diisi kode izin: 1 = IUPHHK-HA 2 = IUPHHBK-HA 3 = IUPHHK-RE 4 = IUPHHK-HTI 5 = IUPHHBK-HT 6 = PENUGASAN 7 = LAINNYA
		jk_waktu	*integer*	3	Diisi masa berlaku izin dengan satuan tahun
		luas_izin	*integer*	10	Diisi luas izin dengan satuan m²
		etat_luas	*integer*	10	diisi luas etat/ AAC (*Annual Allowable Cut*) dengan satuan m²
		etat_vlm	*integer*	10	diisi volume etat/ AAC (*Annual Allowable Cut*) dengan satuan m³
2	*Layer* Kawasan	id_izin	*integer*	10	Tidak diisi karena auto numbering
	Contoh: 123456789876543210_KWS	Nop*)	*text*	18	Diisi Nomor Objek Pajak (NOP)
	Bentuk: Poligon	npwp*)	*text*	15	Diisi Nomor Pokok Wajib Pajak (NPWP)
		luas_kws	*integer*	10	Diisi luas kawasan dengan satuan m² secara sistem
3	*Layer* Areal	nop*)	*text*	18	Diisi NOP
	Contoh: 123456789876543210_ARL	kd_jns_arl*)	*text*	2	Diisi kode jenis areal bumi sebagai berikut: 11 = Areal Produktif Perhutanan 12 = Areal Belum Produktif Perhutanan 13 = Areal Tidak Produktif Perhutanan
	Bentuk: Poligon				

No	Jenis *Layer*	Atribut *Layer*	*Type*	*Length*	Keterangan Pengisian
					14 = Areal Pengaman Perhutanan 15 = Areal Emplasemen Perhutanan 16 = Areal Perlindungan dan Konservasi Perhutanan 21 = Areal Yang Termasuk Objek Pajak Sebagaimana Dimaksud Dalam Pasal 3 Ayat (1) UU PBB 22 = Areal Yang Dipunyai Haknya/Dimanfaatkan Oleh Selain Subjek Pajak/Wajib Pajak
		no_urut*)	*text*	4	Diisi nomor urut secara mandiri dimulai dari bagian kiri atas ke bagian kanan bawah
		luas_arl	*integer*	10	Diisi luas areal dengan satuan m² secara sistem
		uraian	*text*	100	Diisi informasi tambahan yang dianggap perlu, antara lain: nama blok tebangan, jenis hasil hutan kayu, jenis hasil hutan bukan kayu, dan/atau informasi lain yang diperlukan
4	*Layer* RKT Contoh: 123456789876543210_RKT Bentuk: Poligon	id_izin	*integer*	10	Tidak diisi karena *auto numbering*
		id_rkt	*integer*	10	Tidak diisi karena *auto numbering*
		tahun*)	*text*	4	Diisi Tahun Tebang
		luas_rkt	*integer*	10	Diisi luas RKT dengan satuan m² secara sistem
		uraian	*text*	100	Diisi informasi tambahan yang dianggap perlu, antara lain: nama blok tebangan, jenis hasil hutan kayu, jenis hasil hutan bukan kayu, dan/atau informasi lain yang diperlukan

Keterangan:
*) atribut peta yang wajib diisi

b. Hutan Tanaman

No	Jenis *Layer*	Atribut *Layer*	*Type*	*Length*	Keterangan Pengisian
1	*Layer* Izin	id_izin	*integer*	10	Tidak diisi karena *auto numbering*
		nm_pmg_izn	*text*	64	Diisi nama pemegang izin
	Contoh: 123_IZN	no_izin	*text*	64	Diisi nomor izin
	(Disediakan oleh KPDJP)	tgl_izin	*text*	10	Diisi tanggal izin dengan format dd/mm/yyyy
	Bentuk: Poligon	kd_jns_izn	*integer*	1	Diisi kode izin: 1 = IUPHHK-HA 2 = IUPHHBK-HA 3 = IUPHHK-RE 4 = IUPHHK-HTI 5 = IUPHHBK-HT 6 = PENUGASAN 7 = LAINNYA
		jk_waktu	*integer*	3	Diisi masa berlaku izin dengan satuan tahun
		luas_izin	*integer*	10	Diisi luas izin dengan satuan m²
		etat_luas	*integer*	10	diisi luas etat/ AAC (*Annual Allowable Cut*) dengan satuan m²
		etat_vlm	*integer*	10	diisi volume etat/ AAC (*Annual Allowable Cut*) dengan satuan m³
2	*Layer* Kawasan	id_izin	*integer*	10	Tidak diisi karena *auto numbering*
	Contoh: 123456789876543210_KWS	nop*)	*text*	18	Diisi Nomor Objek Pajak (NOP)
	Bentuk: Poligon	npwp*)	*text*	15	Diisi Nomor Pokok Wajib Pajak (NPWP)
		luas_kws	*integer*	10	Diisi luas kawasan dengan satuan m² secara sistem
3	*Layer* Areal	nop*)	*text*	18	Diisi NOP
	Contoh: 123456789876543210_ARL	kd_jns_arl*)	*text*	2	Diisi kode jenis areal bumi sebagai berikut: 11 = Areal Produktif Perhutanan 12 = Areal Belum Produktif Perhutanan 13 = Areal Tidak Produktif Perhutanan 14 = Areal Pengaman Perhutanan 15 = Areal Emplasemen Perhutanan 16 = Areal Perlindungan dan Konservasi Perhutanan
	Bentuk: Poligon				

No	Jenis *Layer*	Atribut *Layer*	*Type*	*Length*	Keterangan Pengisian
					21 = Areal Yang Termasuk Objek Pajak Sebagaimana Dimaksud Dalam Pasal 3 Ayat (1) UU PBB 22 = Areal Yang Dipunyai Haknya/Dimanfaatkan Oleh Selain Subjek Pajak/Wajib Pajak
		no_urut*)	*text*	4	Diisi nomor urut secara mandiri dimulai dari bagian kiri atas ke bagian kanan bawah
		luas_arl	*integer*	10	Diisi luas areal dengan satuan m² secara sistem
		uraian	*text*	100	Diisi informasi tambahan yang dianggap perlu, antara lain: nama blok tebangan, nama kelas hutan, dan/atau informasi lain yang diperlukan
4	*Layer* Areal Tanam Contoh: 123456789876543210_TNM Bentuk: Poligon	nop*)	*text*	18	Diisi NOP
		kd_jns_arl*)	*text*	2	Diisi kode jenis areal bumi sebagai berikut: 11 = Areal Produktif Perhutanan 12 = Areal Belum Produktif Perhutanan 13 = Areal Tidak Produktif Perhutanan 14 = Areal Pengaman Perhutanan 15 = Areal Emplasemen Perhutanan 16 = Areal Perlindungan dan Konservasi Perhutanan 21 = Areal Yang Termasuk Objek Pajak Sebagaimana Dimaksud Dalam Pasal 3 Ayat (1) UU PBB 22 = Areal Yang Dipunyai Haknya/Dimanfaatkan Oleh Selain Subjek Pajak/Wajib Pajak
		no_urut*)	*text*	4	Diisi nomor urut secara mandiri dimulai dari bagian kiri atas ke bagian kanan bawah
		th_tanam*)	*text*	4	Diisi Tahun Tanam
		kd_jns_tnm*)	*text*	2	Diisi kode jenis tanaman sebagai berikut:

No	Jenis *Layer*	Atribut *Layer*	*Type*	*Length*	Keterangan Pengisian
					01 = JELUTUNG/ PULAI 02 = ROTAN 03 = SENGON 04 = JABON 05 = AKASIA 06 = JATI 07 = KARET 08 = KELAPA 09 = SAGU 10 = MAHONI 11 = EUKALIPTUS 12 = PINUS 13 = KAYU PUTIH 14 = JATIPUTIH/GMELINA 15 = DAMAR 16 = WARU GUNUNG/ WARU 17 = KELAPA SAWIT 18 = MINDI 19 = JOHAR 20 = SONOKELING/ SONOBRIT 21 = MERBAU 22 = KERUING 23 = KAMPER 24 = KAPUK RANDU 25 = ANGSANA 26 = BALSA 27 = SUNGKAI/ JATI SABRANG/ JATI LONDO 28 = SONOKEMBANG 29 = KEMIRI 30 = MERANTI 31 = LAMTOROGUNG 32 = ALBASIA/ WERU/ SENGON 33 = PILANG 34 = AKOR 35 = KALIANDRA 36 = KOPI 37 = KAKAO 38 = GAMAL 39 = AREN 40 = CENGKEH

No	Jenis *Layer*	Atribut *Layer*	*Type*	*Length*	Keterangan Pengisian
					41 = MAHANG PUTIH 42 = JABON MERAH 43 = BAMBU 44 = PUSPA 45 = GURICIDIA 46 = EBONI 47 = GAHARU 48 = GULTAPERCA 49 = MAKADAMIA 50 = RASAMALA 51 = CEMARA 52 = JENITRI 53 = NYAMPLUNG 54 = MIMBO 55 = SUREN 56 = BINTAMIN 57 = CYCLO 58 = KESAMBI 59 = BUNGUR 60 = PONTO 61 = PALADO 62 = TEBU 63 = MAESOPSIS EMINII (KAYU AFRIKA) 64 = INGAS 65 = MURBEI 66 = KEPOH 67 = WUNGU 68 = GEMPOL 69 = MANGGA 70 = TENGKAWANG 71 = TRISTANIA 72 = TREMA 73 = METE 74 = JARANAN/KUDO 75 = TANJANG/BAKAU 76 = KEDAWUNG 77 = TREMBESI 78 = PASANG 79 = SONOSISO 80 = KAYU MERAH 81 = SEGAWE

No	Jenis *Layer*	Atribut *Layer*	*Type*	*Length*	Keterangan Pengisian
					82 = WALIKUKUN 83 = SAWO 84 = CENDANA 85 = CIPRUS 86 = RUMPUT GAJAH 87 = INDIGOFERA 88 = MELANGIR/ MERANTI MERAH 89 = NYATOH 90 = SINGKONG 91 = KESEMEK
		luas_tnm	*integer*	10	Diisi luas areal tanam dengan satuan m² secara sistem
		uraian	*text*	100	Diisi informasi tambahan yang dianggap perlu, antara lain: nama blok tebangan, nama kelas hutan, dan/atau informasi lain yang diperlukan
5	*Layer* RKT Contoh: 123456789876543210_RKT Bentuk: Poligon	id_izin	*integer*	10	Tidak diisi karena *auto numbering*
		id_rkt	*integer*	10	Tidak diisi karena *auto numbering*
		tahun*)	*text*	4	Diisi Tahun Tanam atau Tahun Tebang/ panen
		luas_rkt*)	*integer*	10	Diisi luas RKT dengan satuan m² secara sistem
		uraian	*text*	100	Diisi informasi tambahan yang dianggap perlu, antara lain: nama blok tebangan, nama kelas hutan, penjelasan atas atribut tahun berupa tahun tanam atau tahun panen, dan/atau informasi lain yang diperlukan. Keterangan Tambahan: Khusus untuk Perum Perhutani, sumber data yang digunakan untuk *Layer* RKT adalah Rencana Teknik Tahunan (RTT)

Keterangan:
*) atribut peta yang wajib diisi

Catatan:
1. CRS dengan WGS 84 EPSG:4326
2. *Length* menunjukkan jumlah *digit* dalam suatu atribut.

2. Contoh Visualisasi Peta Objek Pajak per *Layer*
   a. Hutan Alam
      1) *Layer* Izin

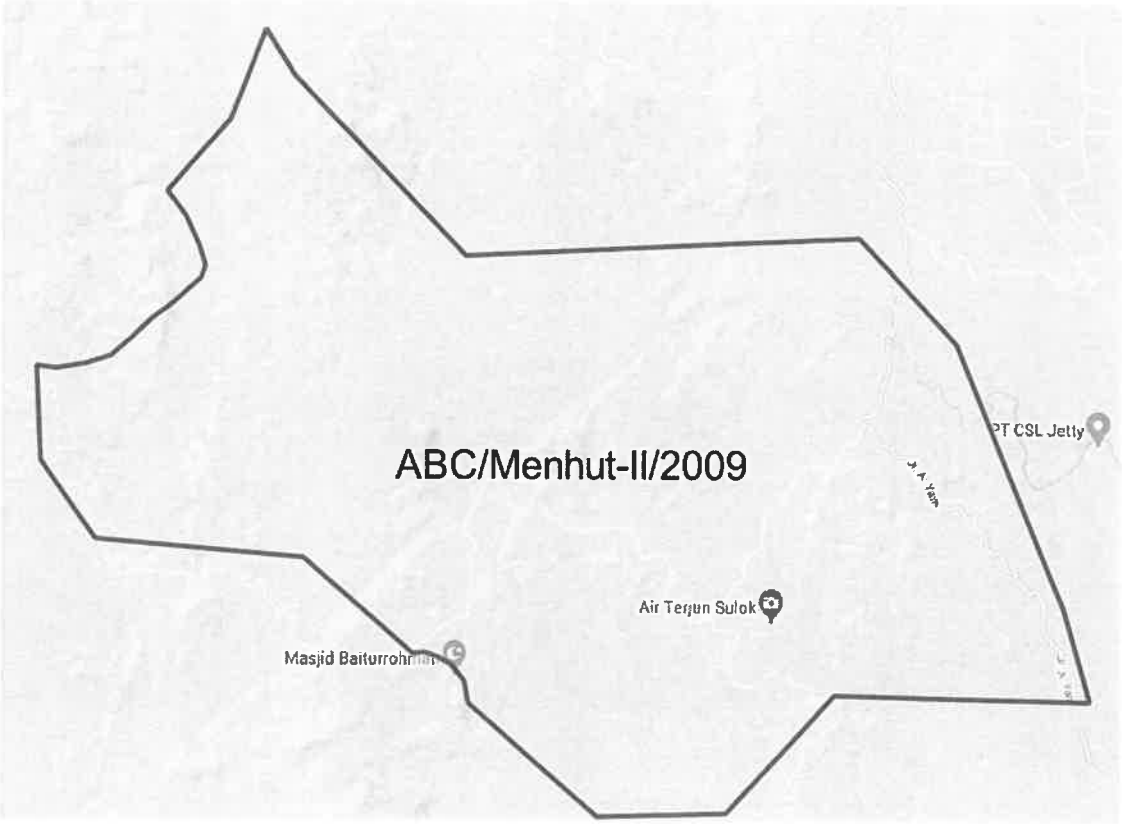

Label: Nomor Izin

2) *Layer* Kawasan

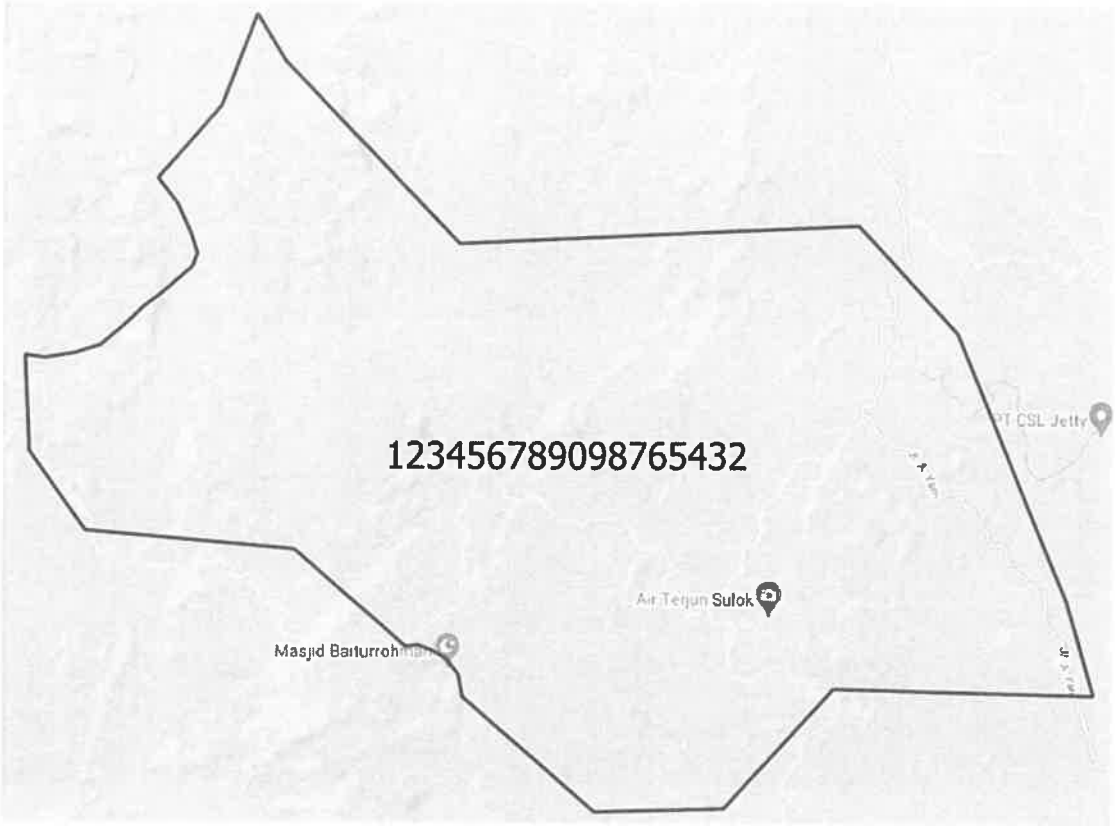

Label: Nomor Objek Pajak (NOP)

3) *Layer* Areal

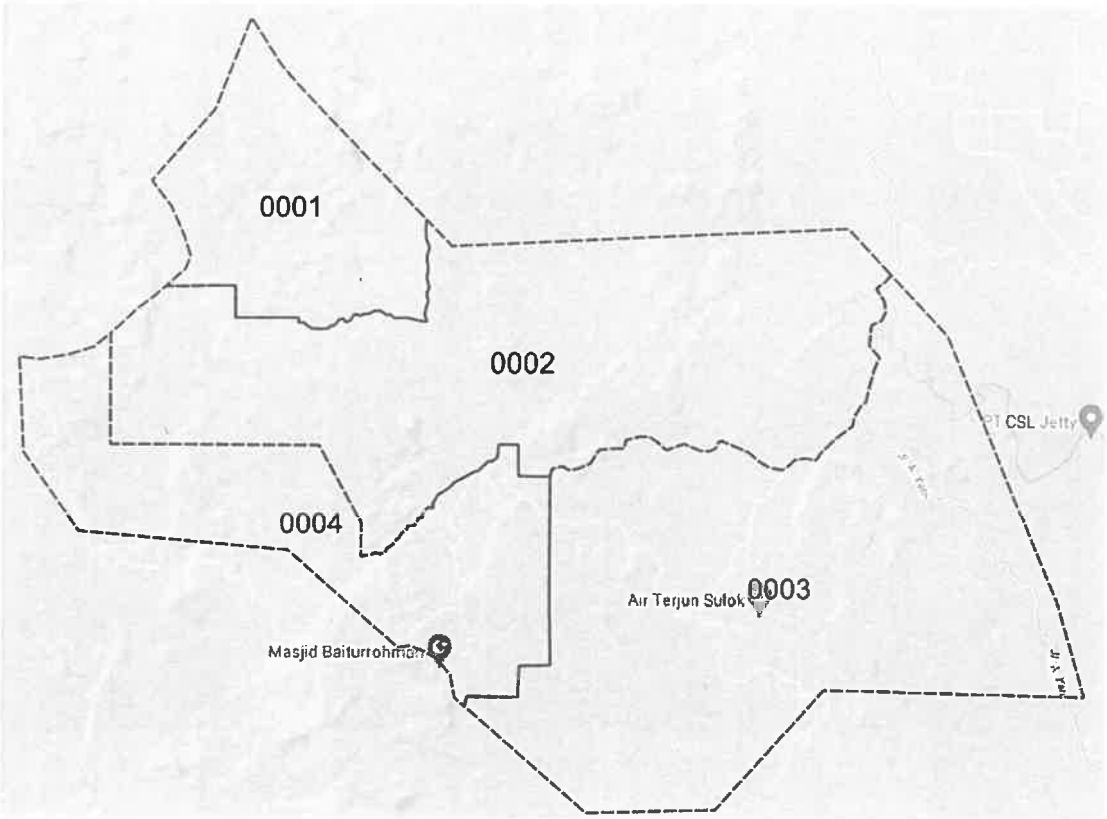

Label: Nomor Urut Areal

4) *Layer* RKT

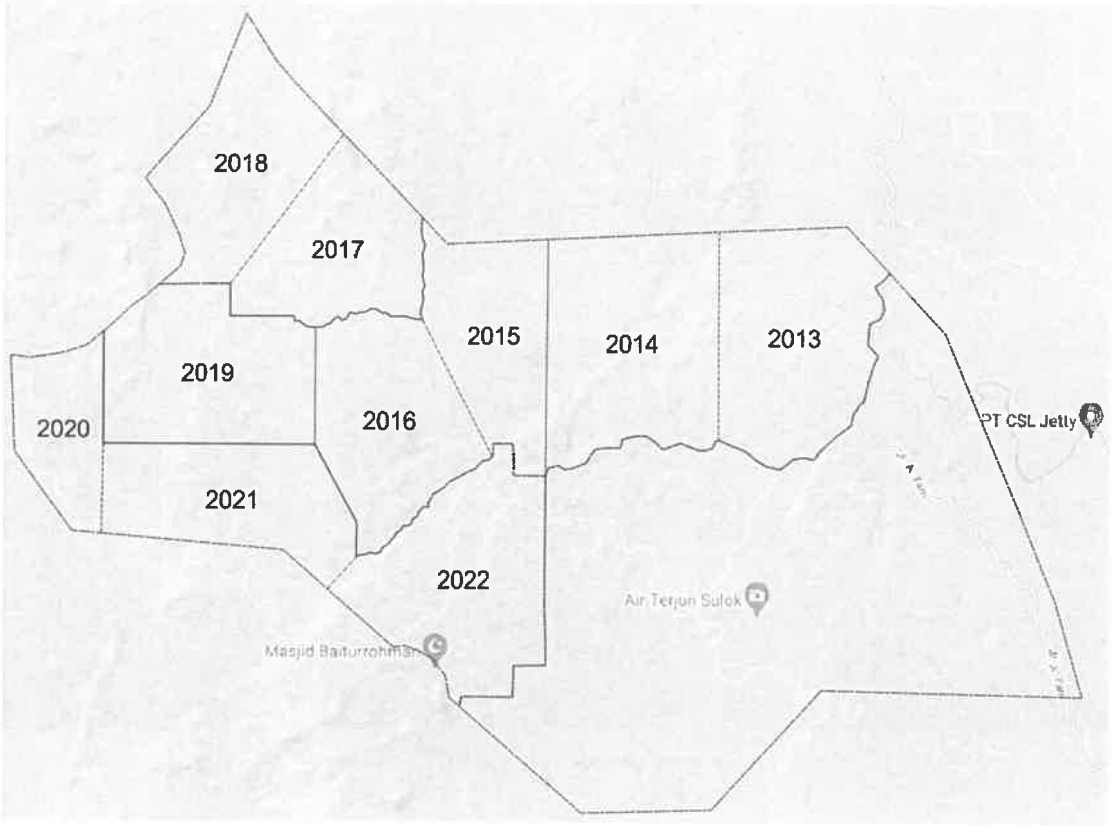

Label: Tahun Tebang

5) Visualisasi 4 (empat) *Layer*

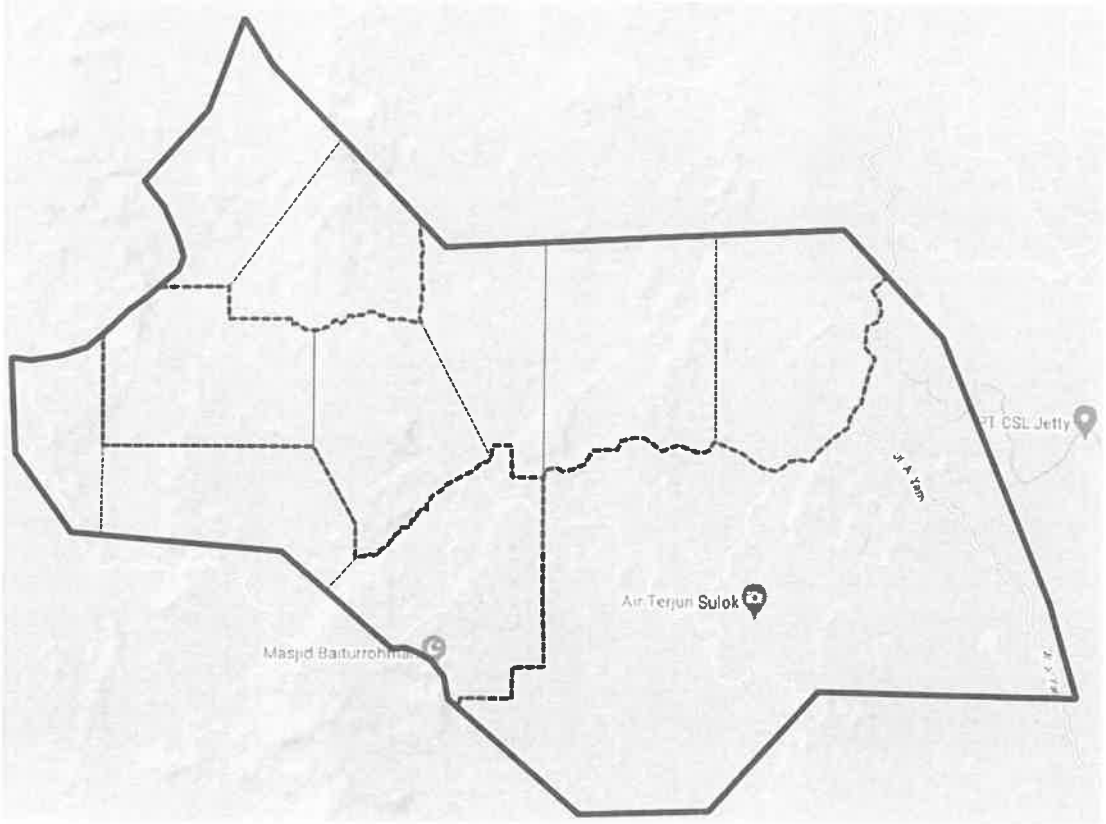

b. Hutan Tanaman

1) *Layer* Izin

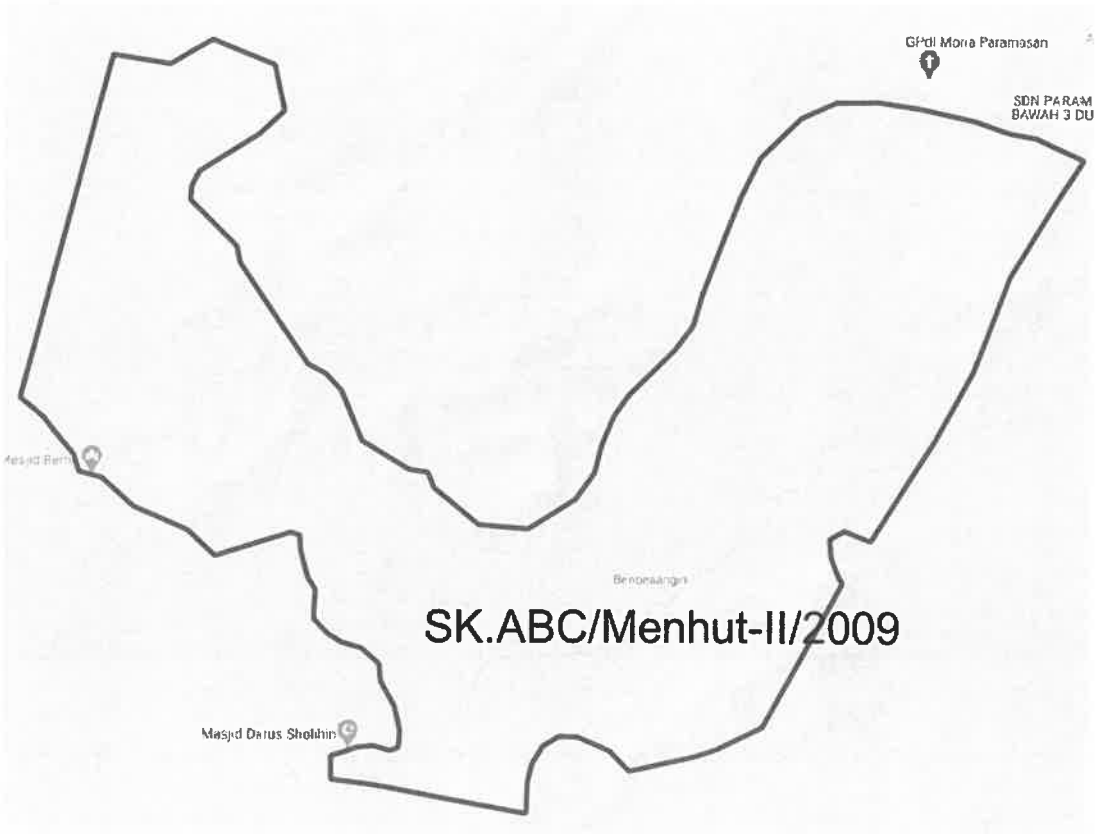

Label: Nomor Izin

2) *Layer* Kawasan

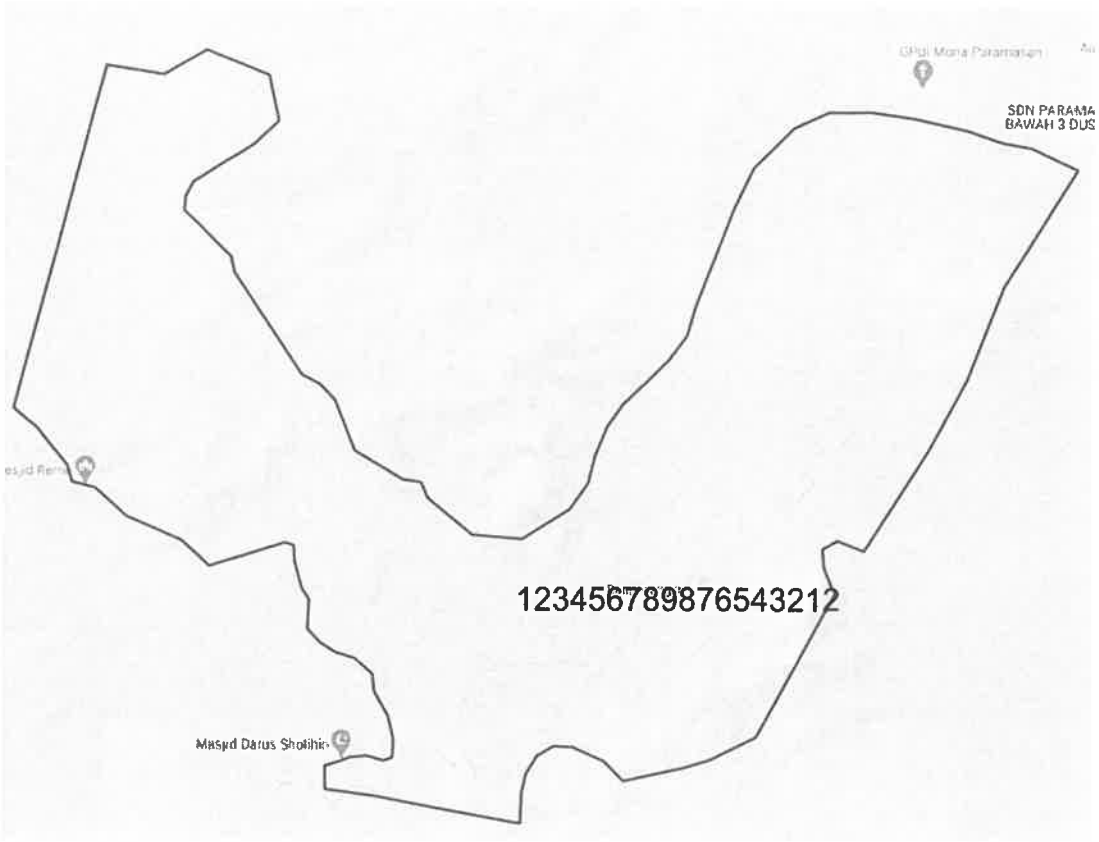

Label: Nomor Objek Pajak (NOP)

3) *Layer* Areal

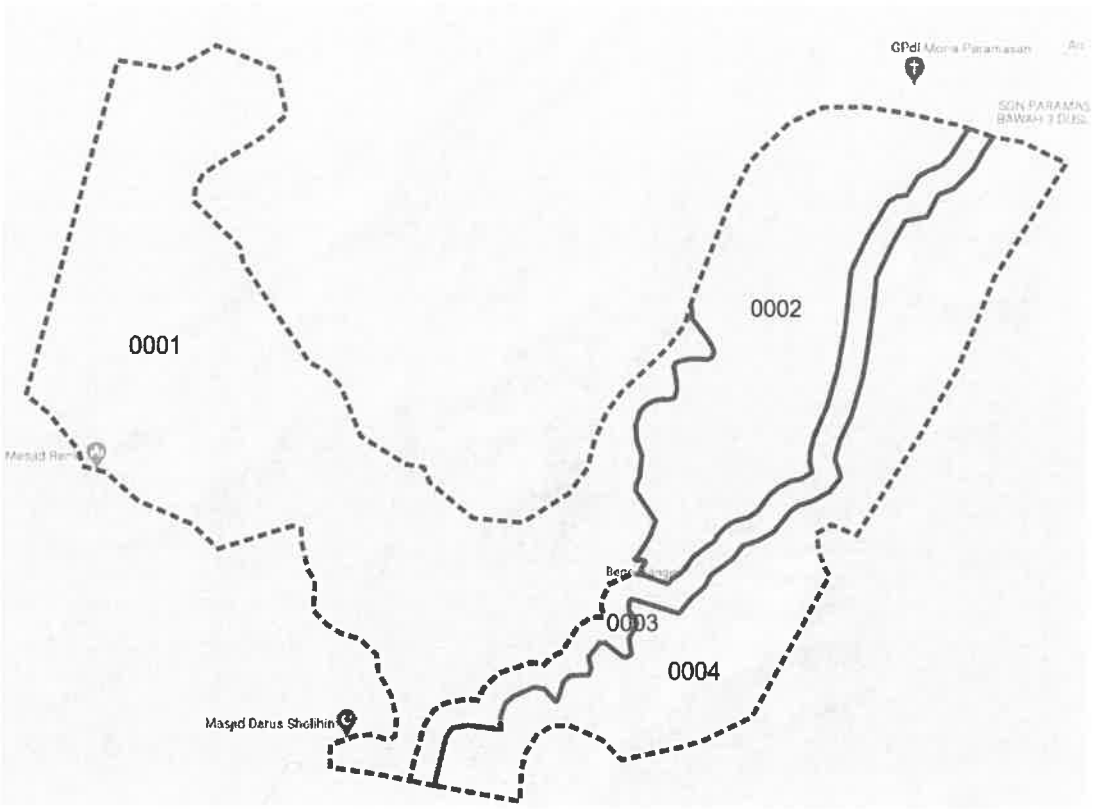

Label: Nomor Urut Areal

4) *Layer* Areal Tanam

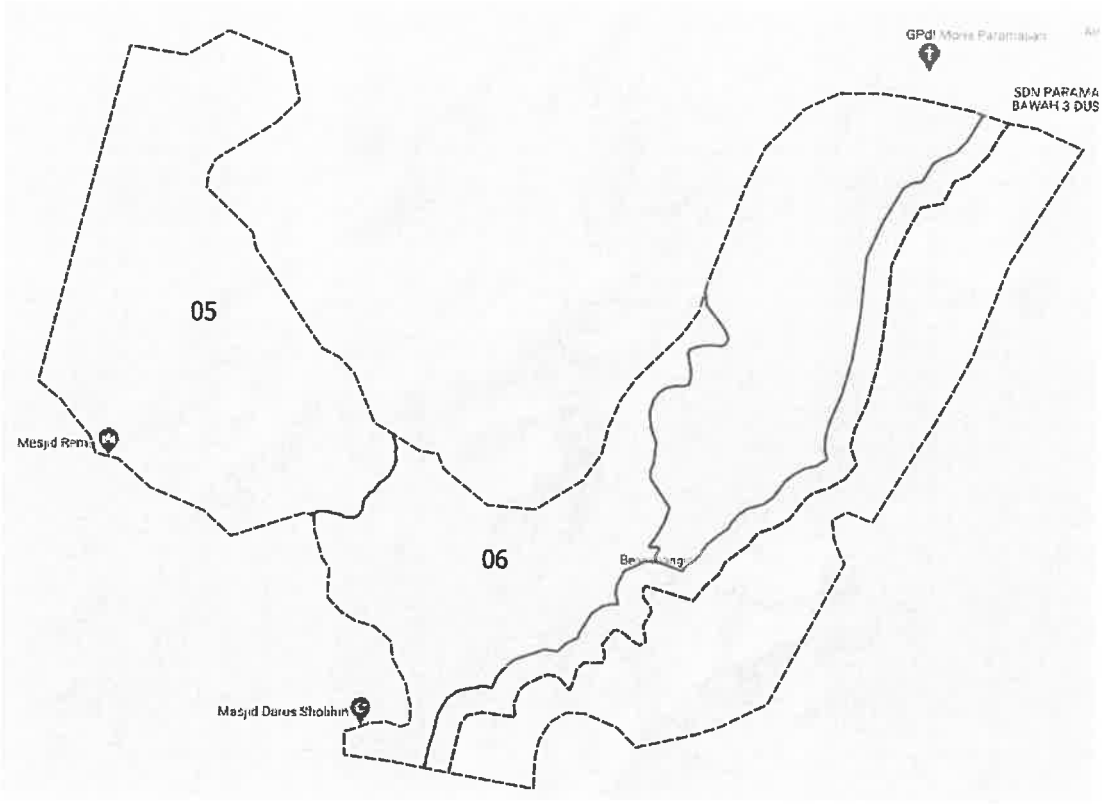

Label: Kode Jenis Tanaman

5) *Layer* RKT

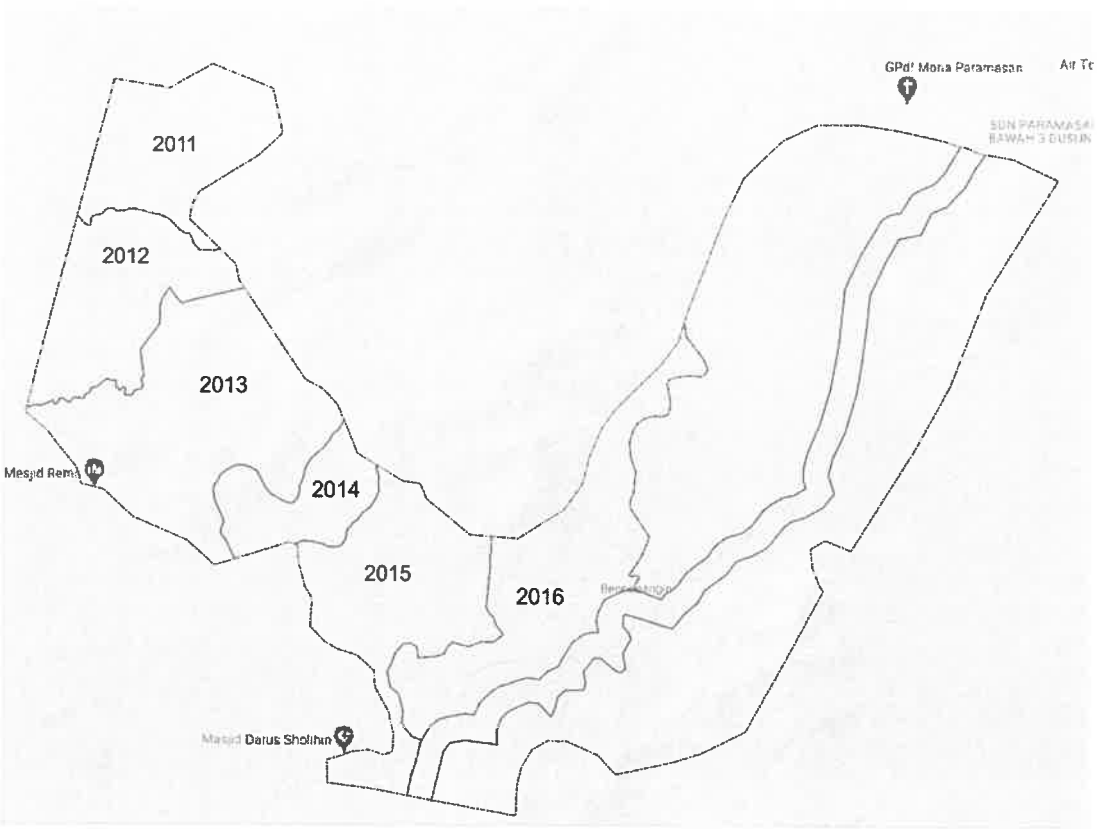

Label: Tahun Tanam

6) Visualisasi 5 (lima) *Layer*

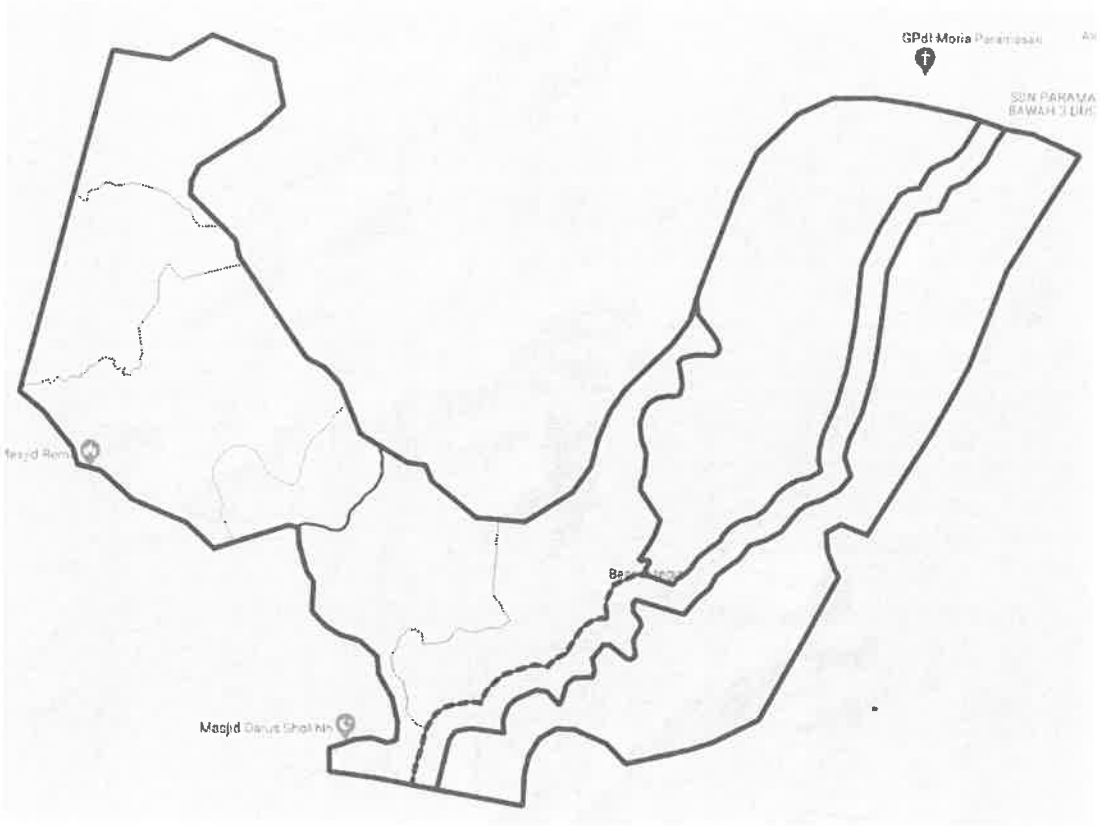

L. PROSEDUR PENGOLAHAN PETA DI KPP

1. Deskripsi
   Prosedur ini menjelaskan tata cara Pengolahan Peta sesuai standar di KPP.

2. Prosedur Kerja
   a. Pelaksana atau *Account Representative* Seksi Pengawasan yang bertindak sebagai koordinator kegiatan Pengumpulan Peta dan Pengolahan Peta menyampaikan Peta Kerja yang diperoleh dari Wajib Pajak kepada Penilai Pajak agar dilakukan Pengolahan Peta sesuai standar yang telah ditentukan.
   b. Penilai Pajak melakukan Pengolahan Peta, atas Peta Kerja yang diperoleh dari Wajib Pajak sesuai standar yang telah ditentukan melalui Registrasi Peta berdasarkan sistem referensi koordinat WGS 84 EPSG:4326, dengan ketentuan:
      1) Hutan Alam, berupa *Layer* Izin, *Layer* Kawasan, *Layer* Areal, dan *Layer* RKT; dan
      2) Hutan Tanaman, berupa *Layer* Izin, *Layer* Kawasan, *Layer* Areal, *Layer* Areal Tanam, dan *Layer* RKT.
   c. Pengolahan Peta sebagaimana dimaksud dalam huruf b dilakukan sebagai berikut:
      1) Peta Kerja yang diperoleh dari Wajib Pajak berupa Peta Raster
         a) Dalam hal atribut dan koordinat Peta Kerja sudah sesuai, maka dilakukan Registrasi Peta Kerja dan digitasi Peta Kerja sesuai standar.
         b) Dalam hal atribut dan koordinat Peta Kerja belum sesuai, maka:
            (1) dilakukan konfirmasi kepada Wajib Pajak atas koordinat dan kelengkapan atribut Peta Kerja (dalam hal atribut Peta Kerja tidak lengkap);
            (2) dilakukan identifikasi lokasi objek pajak berdasarkan desa, kecamatan, atau *landmark* tertentu, apabila Wajib Pajak tidak mengetahui koordinat objek pajak, kemudian dilakukan identifikasi posisi pada citra satelit/Peta dasar;
            (3) dilakukan Registrasi Peta Kerja apabila posisi objek pajak telah teridentifikasi pada citra satelit/Peta dasar; dan
            (4) dilakukan digitasi Peta Kerja sesuai standar.
      2) Peta Kerja yang diperoleh dari Wajib Pajak berupa Peta Vektor
         a) Dalam hal Peta Kerja dengan format *shapefile* (.shp), maka:
            (1) penyesuaian CRS dengan standar yang ditentukan (WGS 84 EPSG:4326); dan
            (2) penyesuaian isian atribut pada *Layer* Peta Kerja dengan standar yang ditentukan.
         b) Dalam hal Peta Kerja dengan format selain *shapefile* (.shp), maka:
            (1) dilakukan konversi Peta Kerja selain format *shapefile* (.shp) menjadi Peta dengan format *shapefile* (.shp);
            (2) penyesuaian CRS dengan standar yang ditentukan (WGS 84 EPSG:4326); dan
            (3) penyesuaian isian atribut pada *Layer* Peta Kerja dengan standar yang ditentukan.
   d. Penilai Pajak mengunggah hasil digitasi Peta Kerja yang sudah sesuai standar ke aplikasi yang telah disediakan oleh DJP.
   e. Proses selesai.

3. Bagan Alir

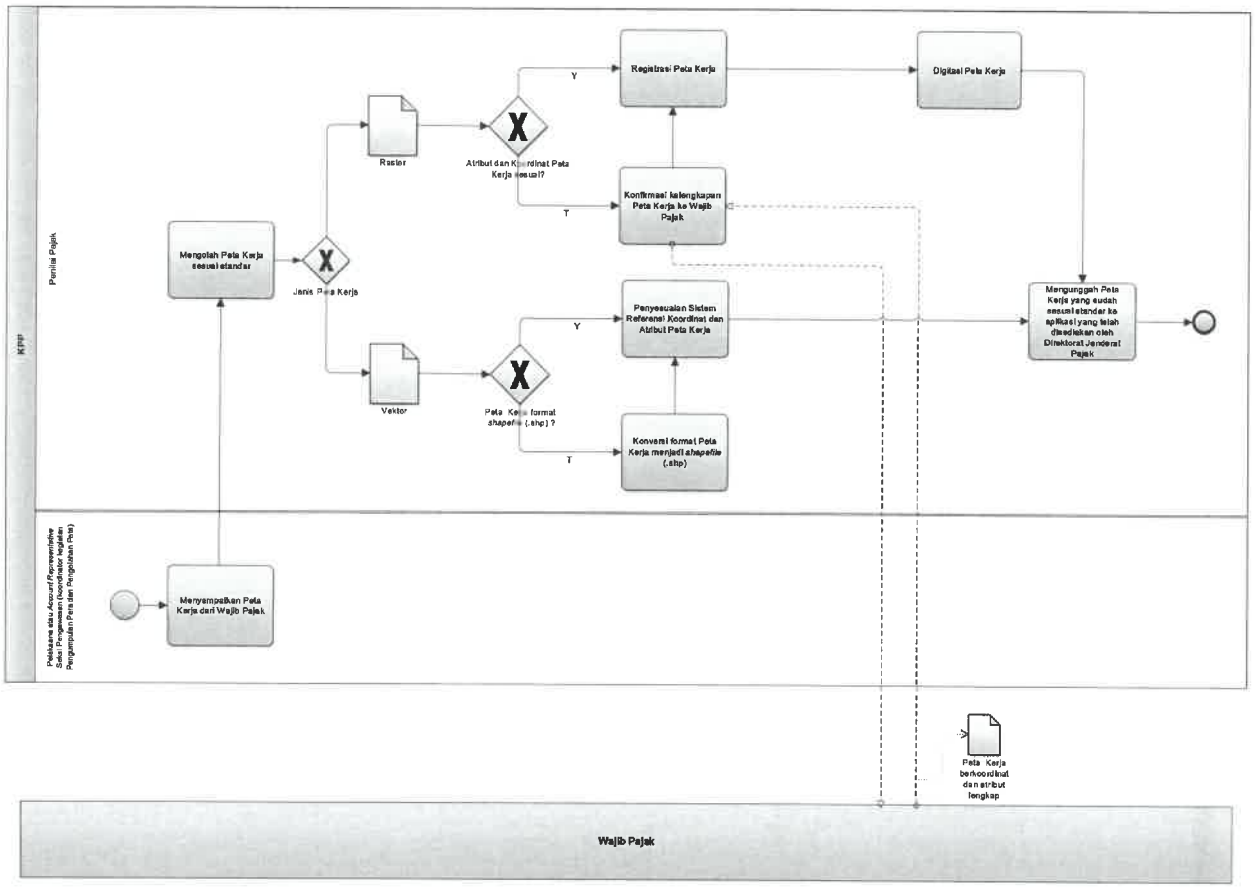

Direktur Jenderal Pajak,

Suryo Utomo